Data Center SCL02 - SCL03

Figura 1-1. Bloques MEGALFLEX

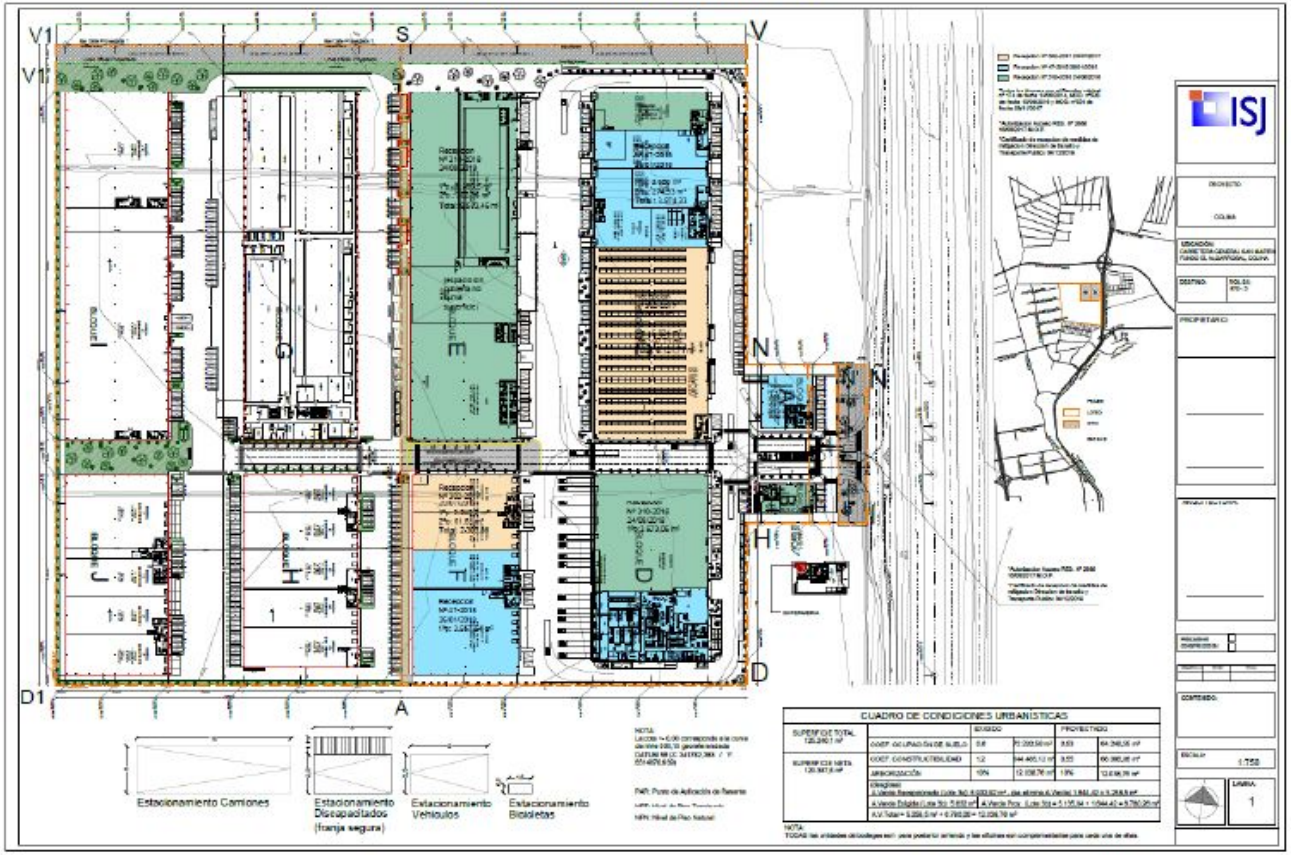

Fuente: Extracto plano "LAM1 MEGAFLEX", Anexo 1.3 de la DIA

Figura 1-2. Ubicación del Proyecto en Datum WGS84

- **A nivel regional**

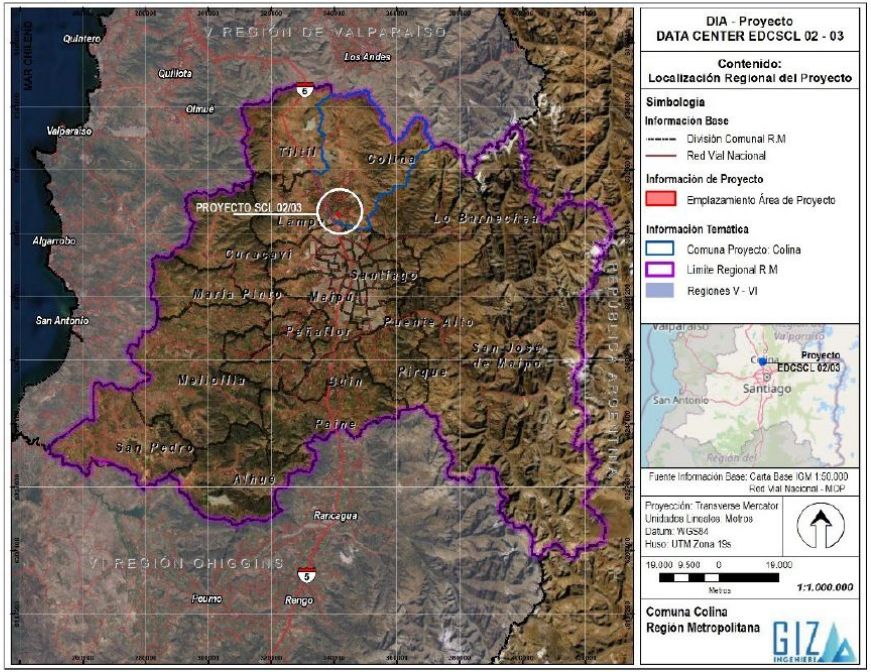

- **A Nivel comunal**

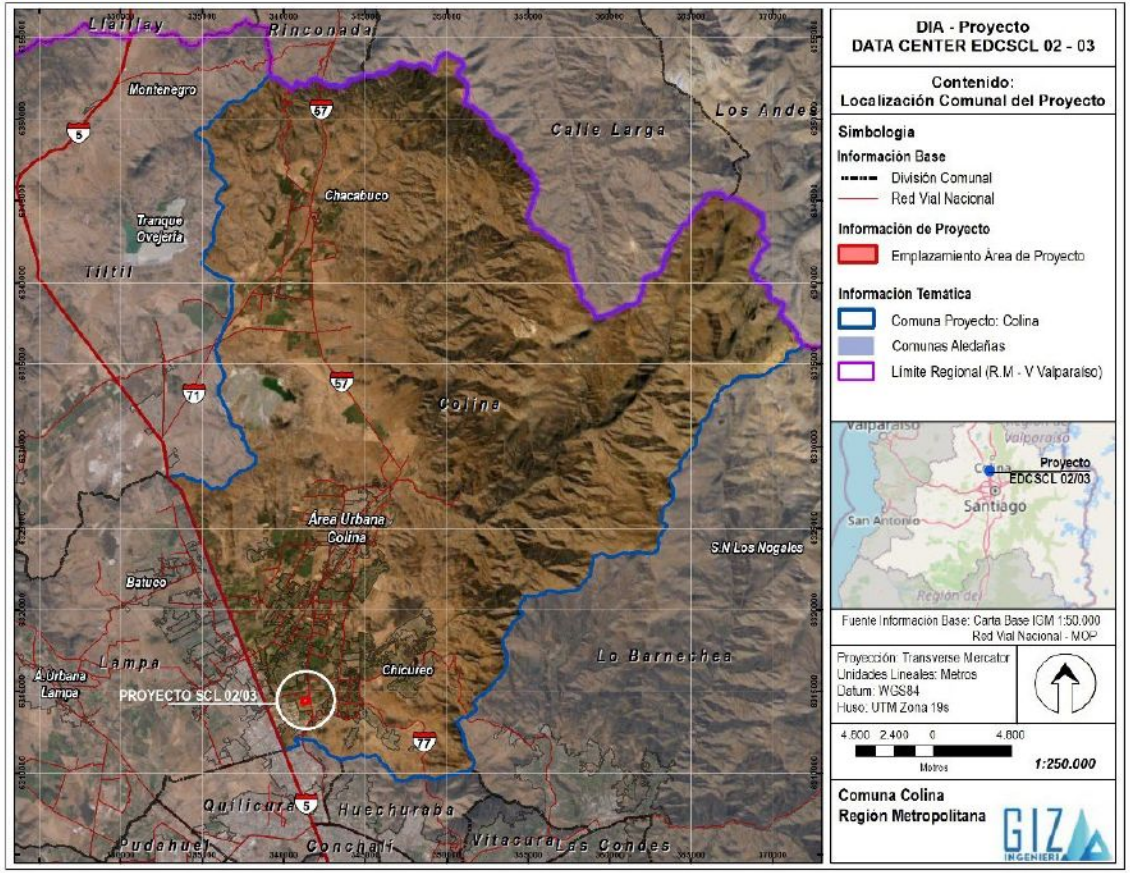

Fuente: Elaboración propia, 2022

Figura 1-3. Acceso al Condominio de bodegas MEGAFLEX

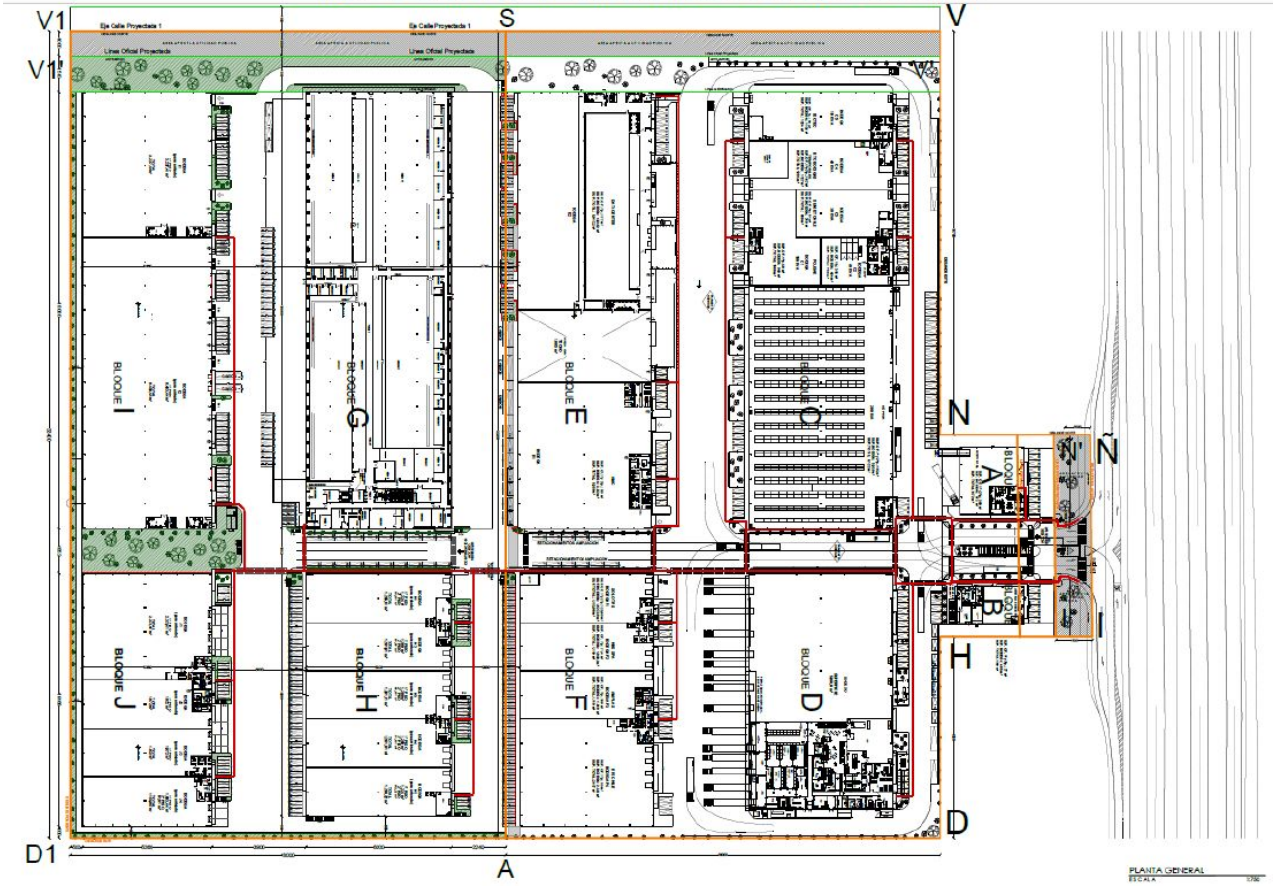

Fuente: Plano "ACCESIBILIDAD", Anexo 1.3 de la DIA

Figura 1-7. Ubicación del Proyecto respecto del PRMS y PRC Colina

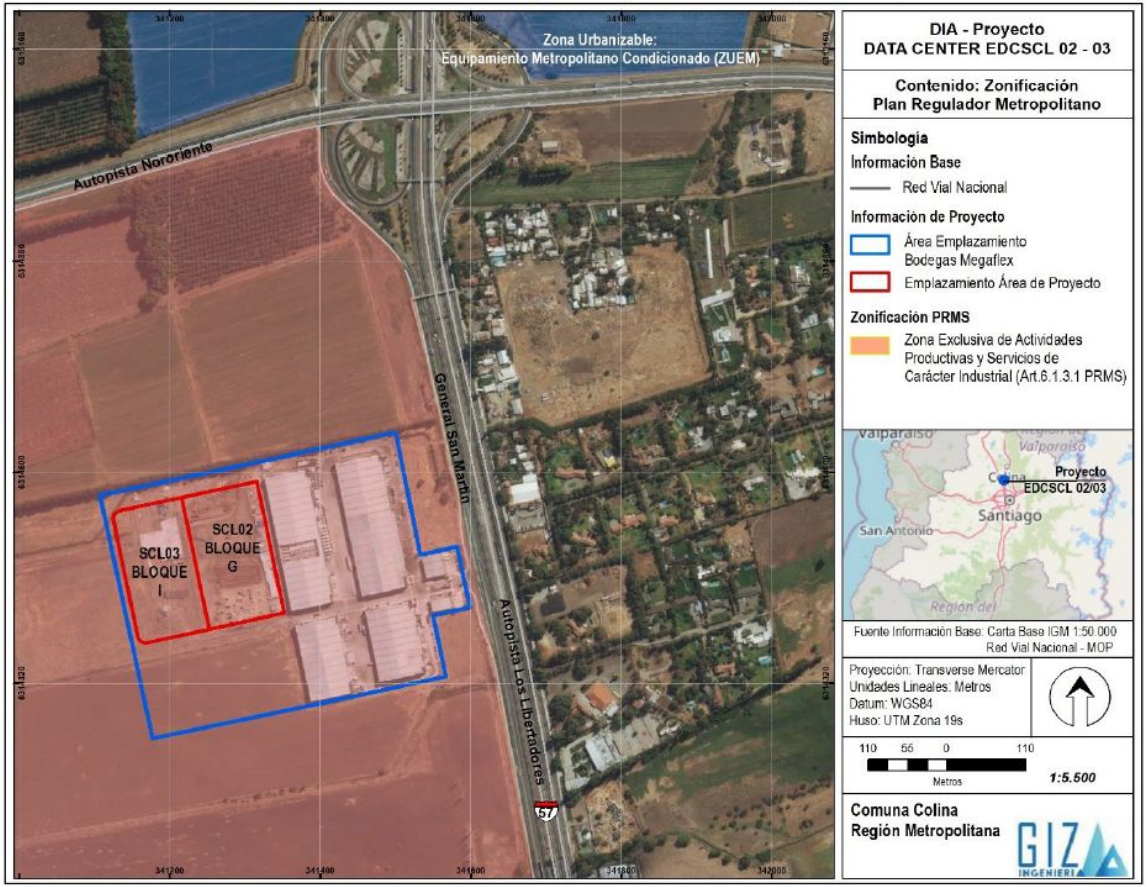

Fuente: Elaboración propia, 2022

Figura 1-9. Obras y partes de la instalación de faenas menores y apoyo de servicios sanitarios

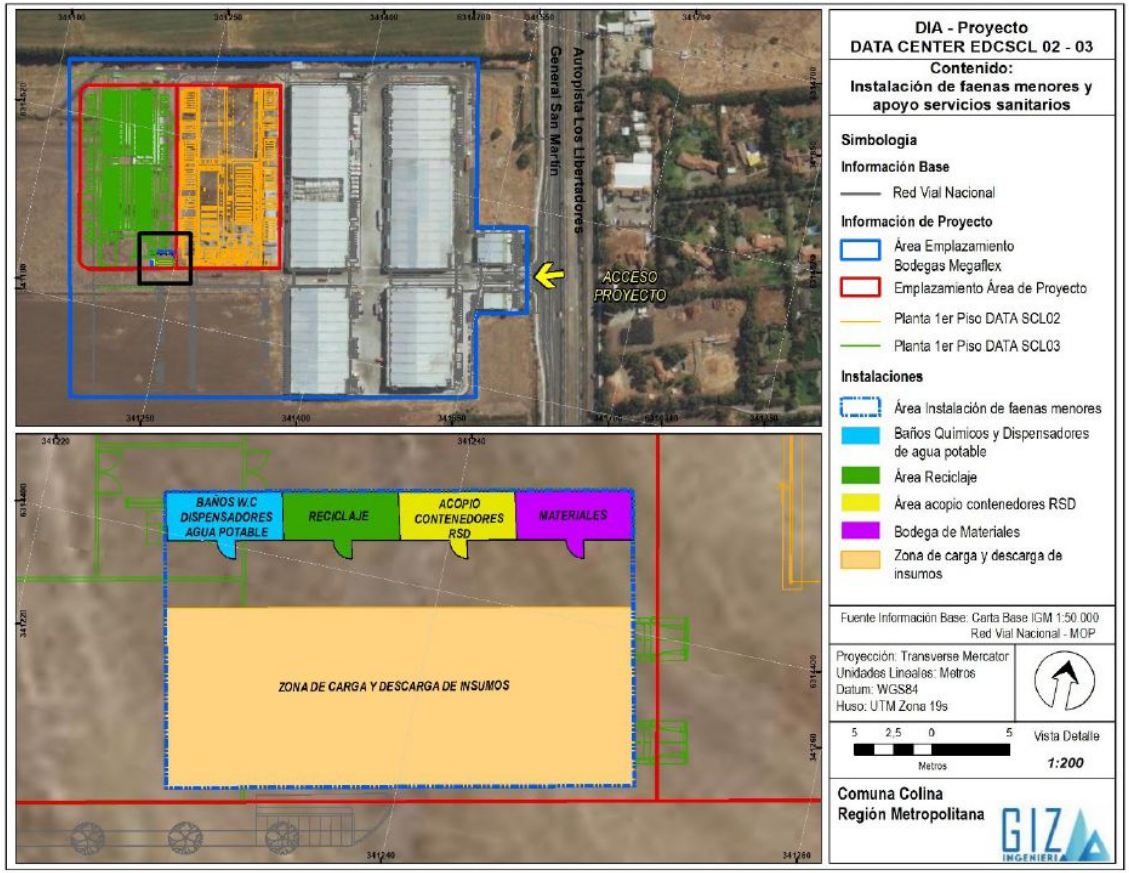

Fuente: Elaboración propia, 2022

Figura 1-10. Layout de los data centers SCL02-SCL03

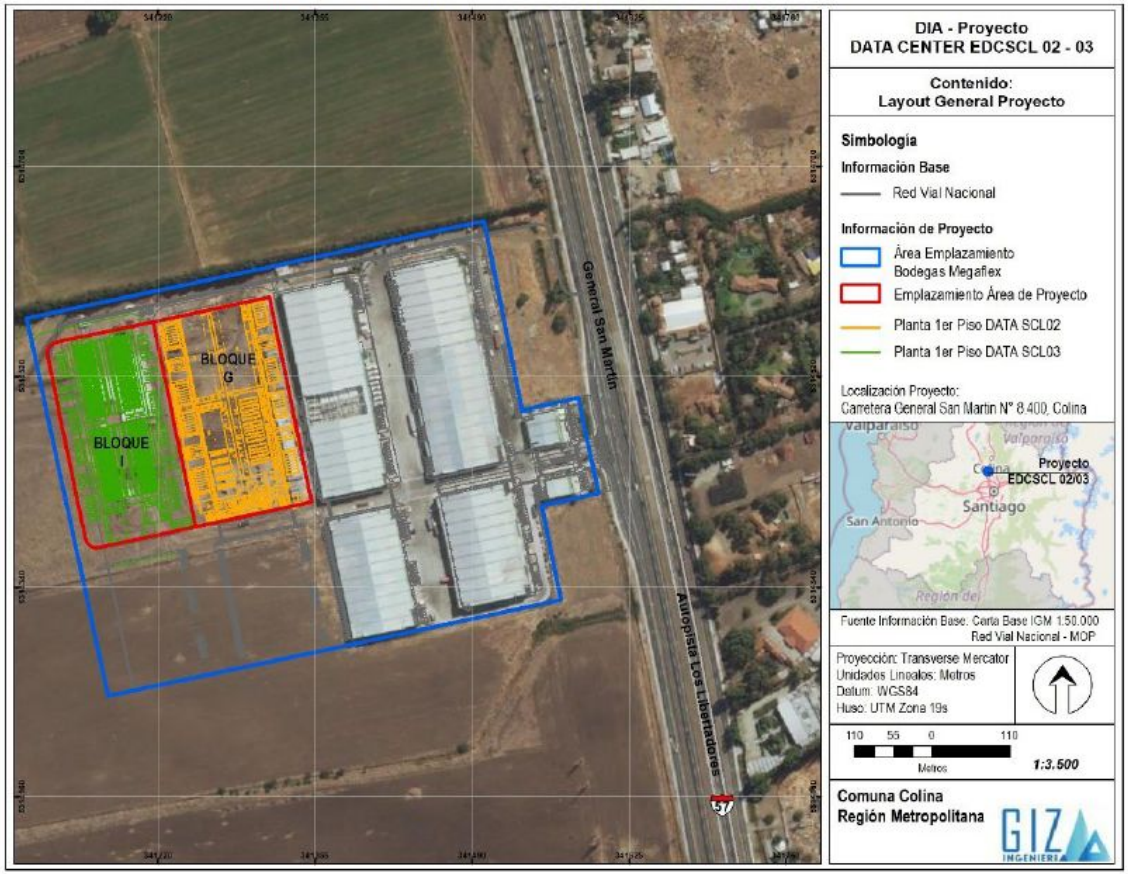

Fuente: Elaboración propia, 2022

Figura 1-11. Planta 1° piso Bloque G

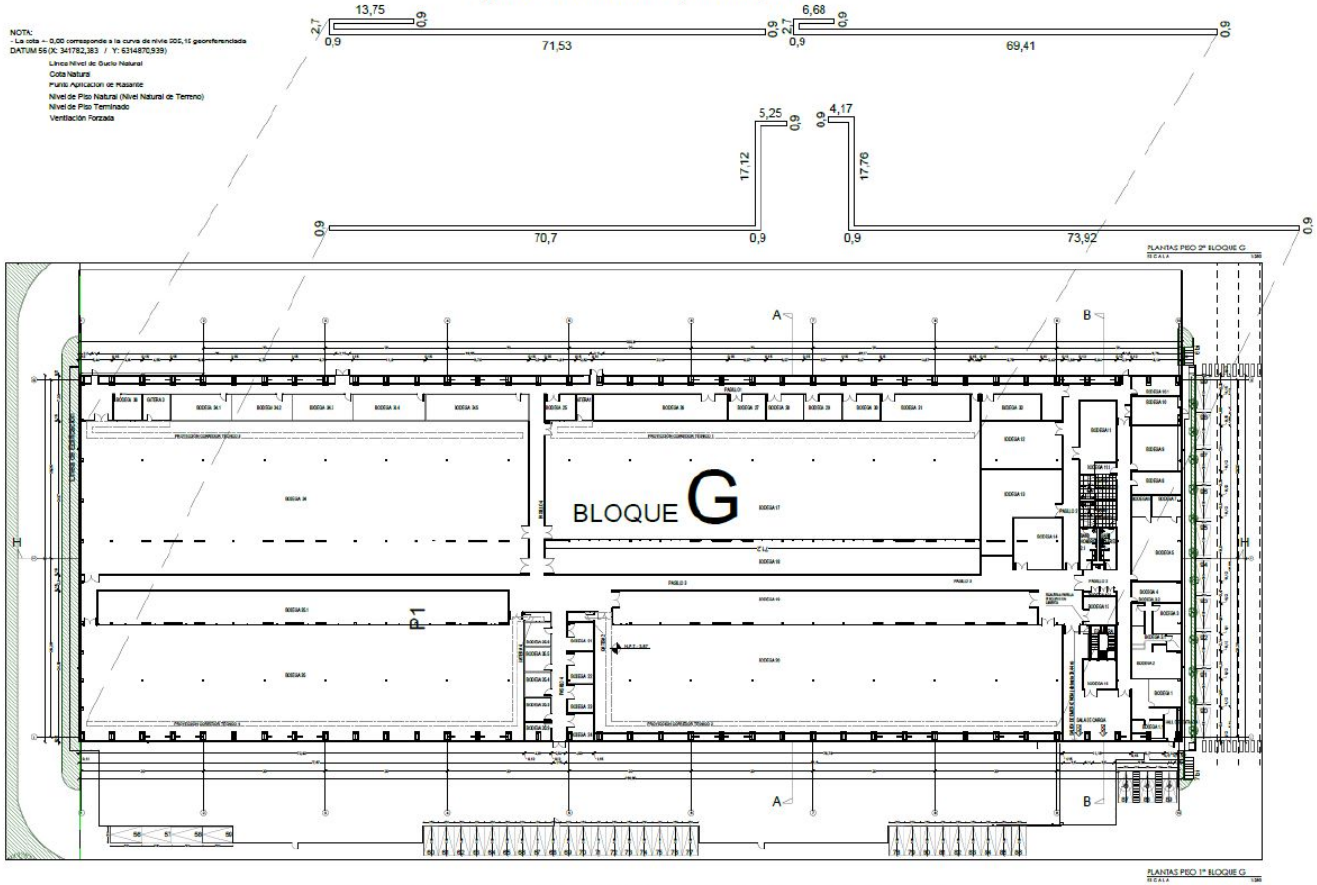

Fuente: Extracto plano "LAM 4 MEGAFLEX", Anexo 1.3 de la DIA

Figura 1-12. Elevaciones Bloque G

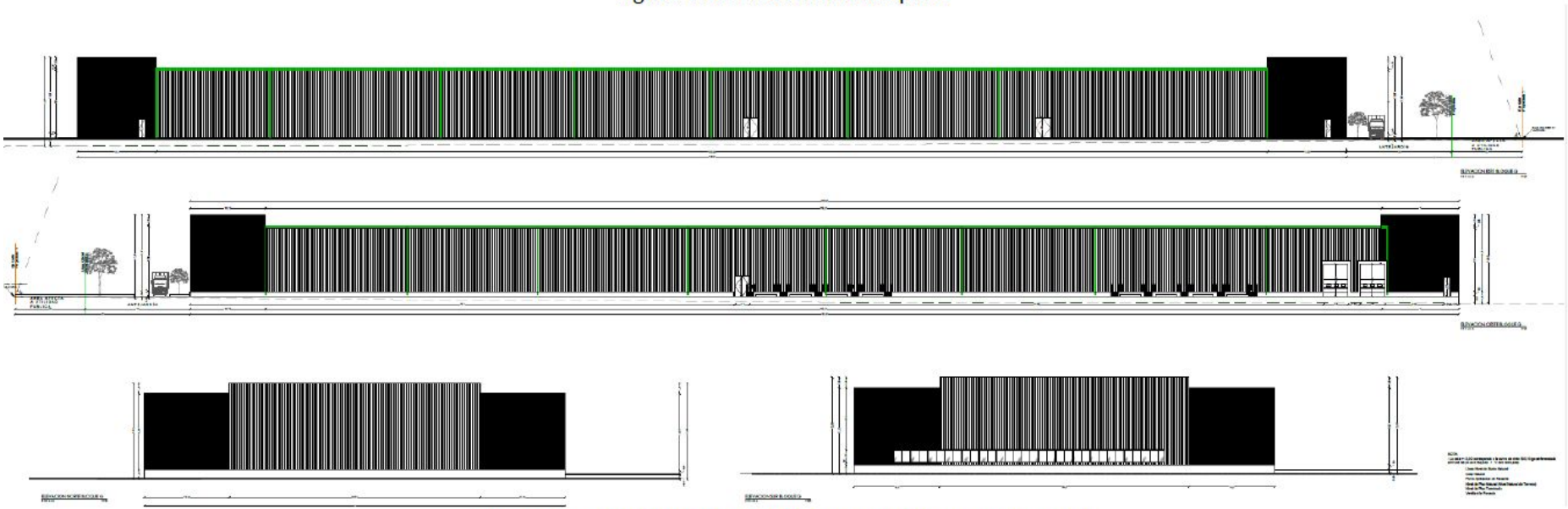

Fuente: Extracto plano “LAM 5 MEGAFLEX”, Anexo 1.3 de la DIA

Figura 1-13. Distribución de las partes y obras del data center SCL02

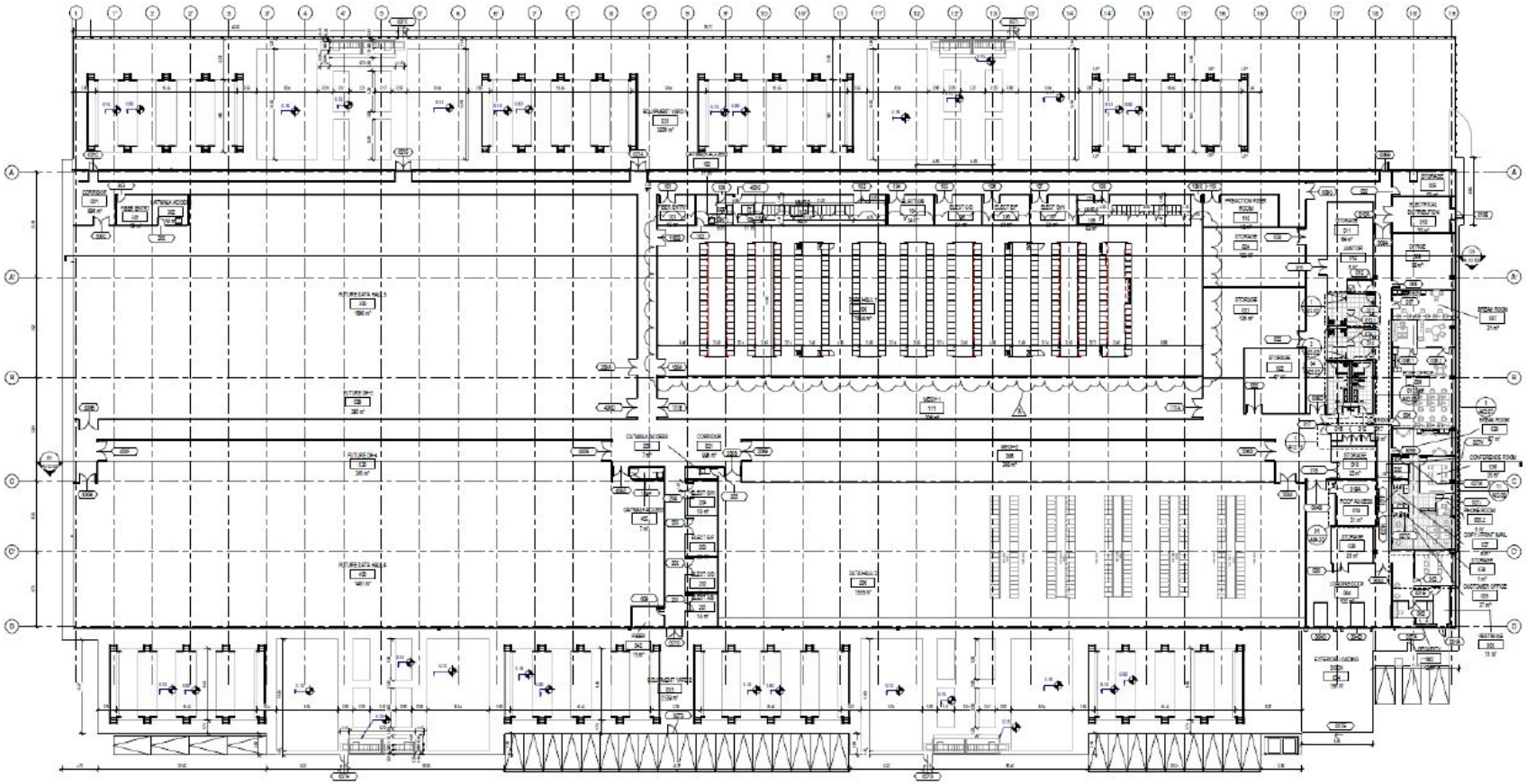

Fuente: Extracto Plano “Distribución SCL02”, Anexo 1.3 de la DIA

Figura 1-14. Planta 1° piso Bloque I

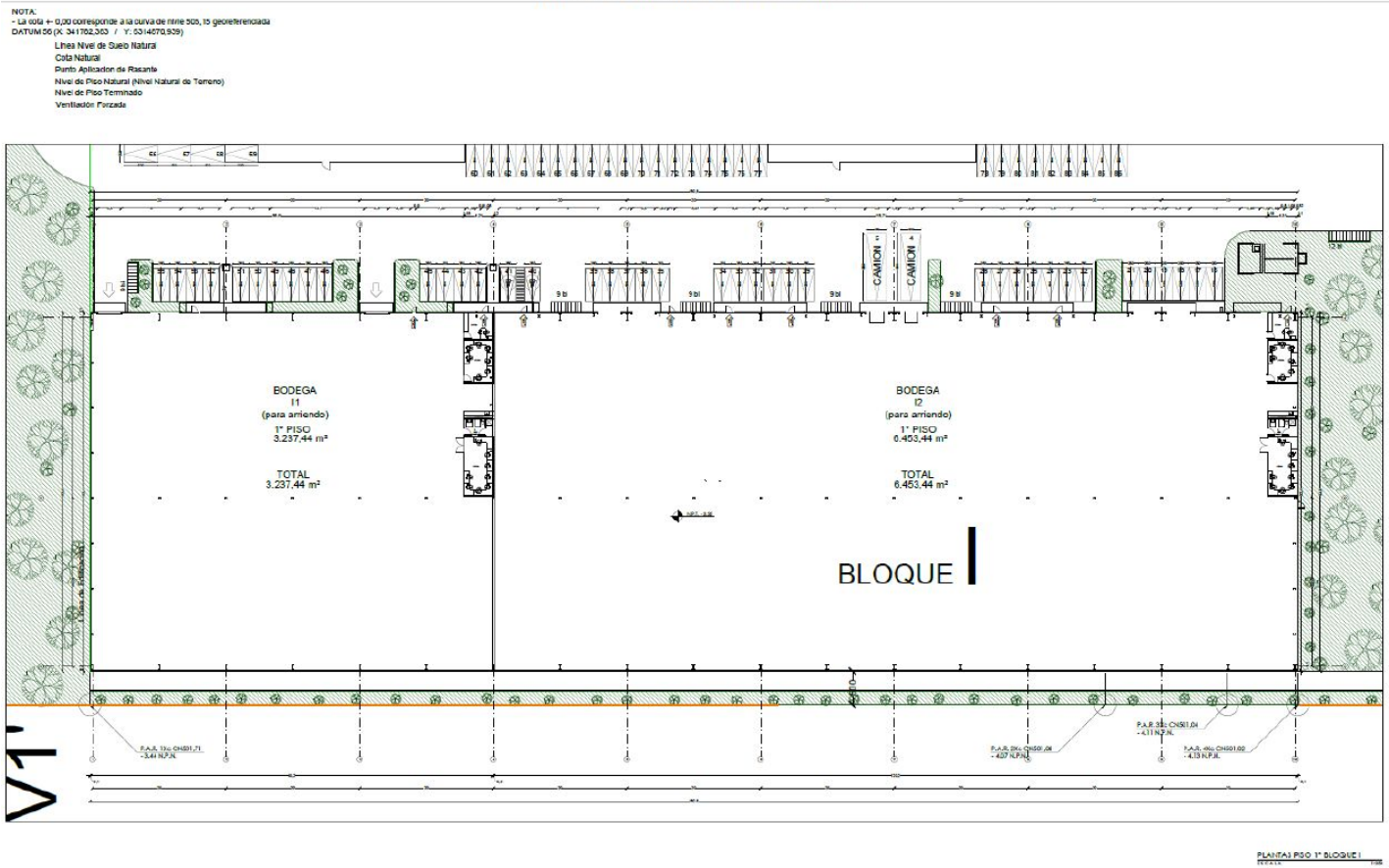

Fuente: Extracto plano "LAM 10 MEGAFLEX", Anexo 1.3 de la DIA

Figura 1-15. Elevaciones Bloque I

Fuente: Extracto plano “LAM 11 MEGAFLEX”, Anexo 1.3 de la DIA

Figura 1-16. Distribución de las partes y obras del data center SCL03

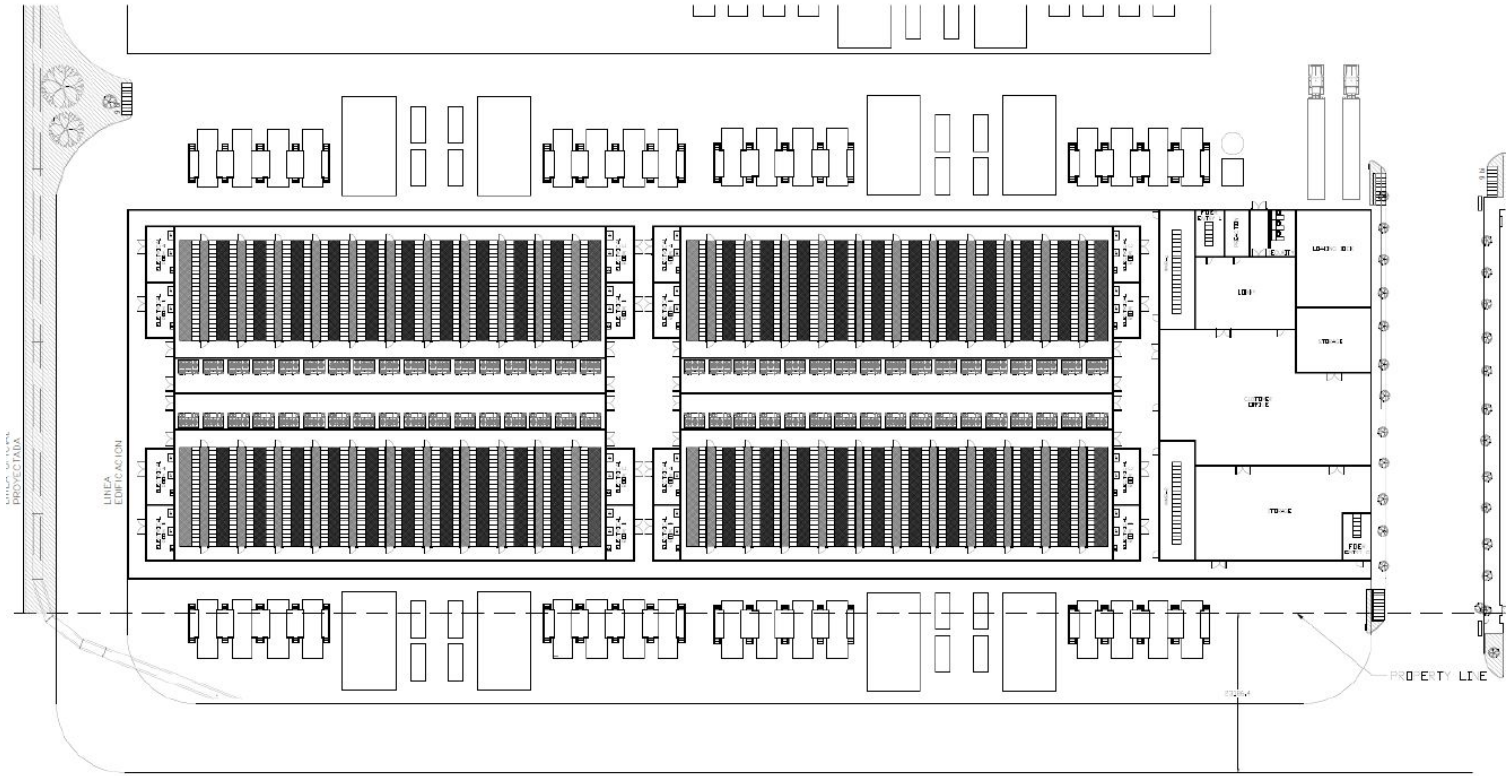

Fuente: Extracto Plano "Distribución SCL03", Anexo 1.3 de la DIA