Data Center SCL04

Figura 1-3. Master plan

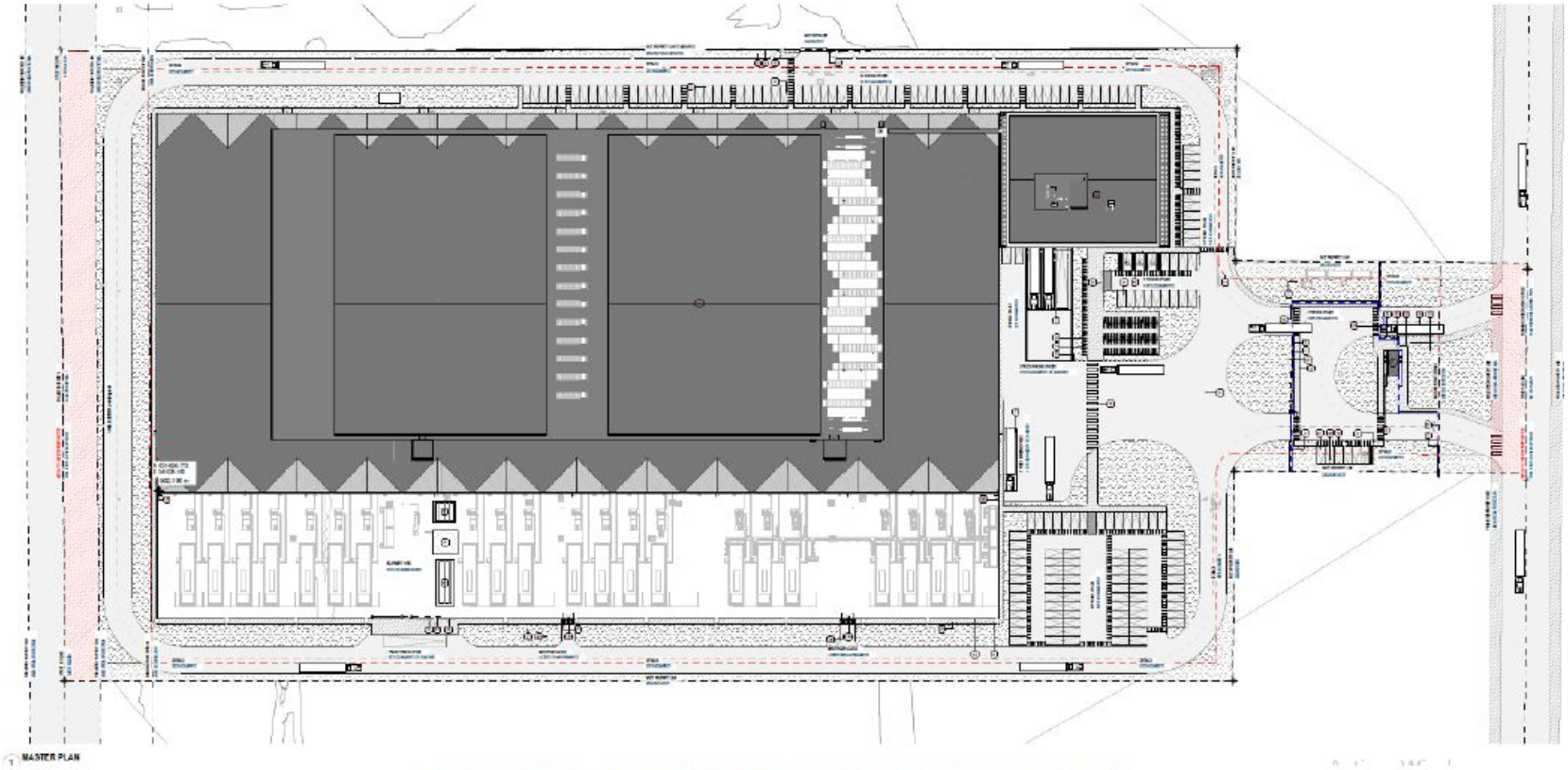

Fuente: SCL04_ARCHITECTURAL SITE PLAN, Anexo 1.3 de la DIA

Figura 1-8. Ubicación del Proyecto respecto del PRMS

Fuente: Elaboración propia, 2023

Figura 1-9. Ubicación del Proyecto respecto del PRC Colina

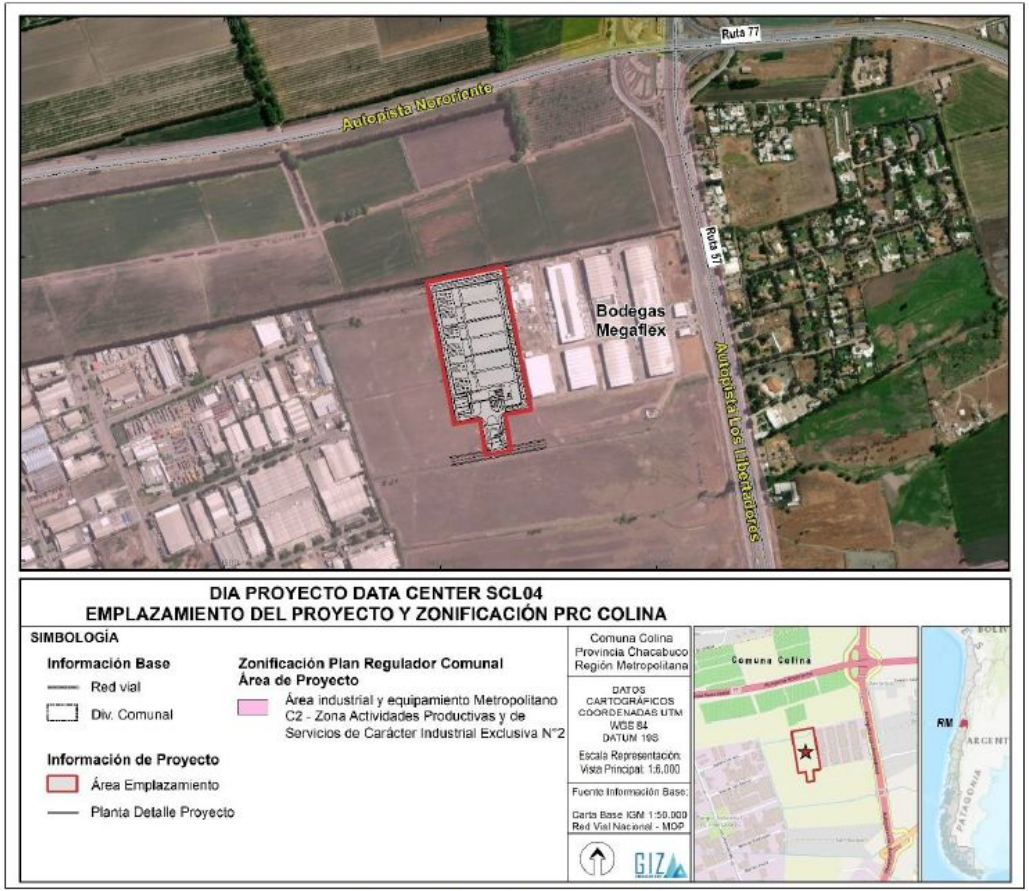

Fuente: Elaboración propia, 2023

Figura 1-18. Bodega de residuos peligrosos (RESPEL)

Fuente: Elaboración propia, 2023

Figura 1-19. Arquitectura del edificio data center

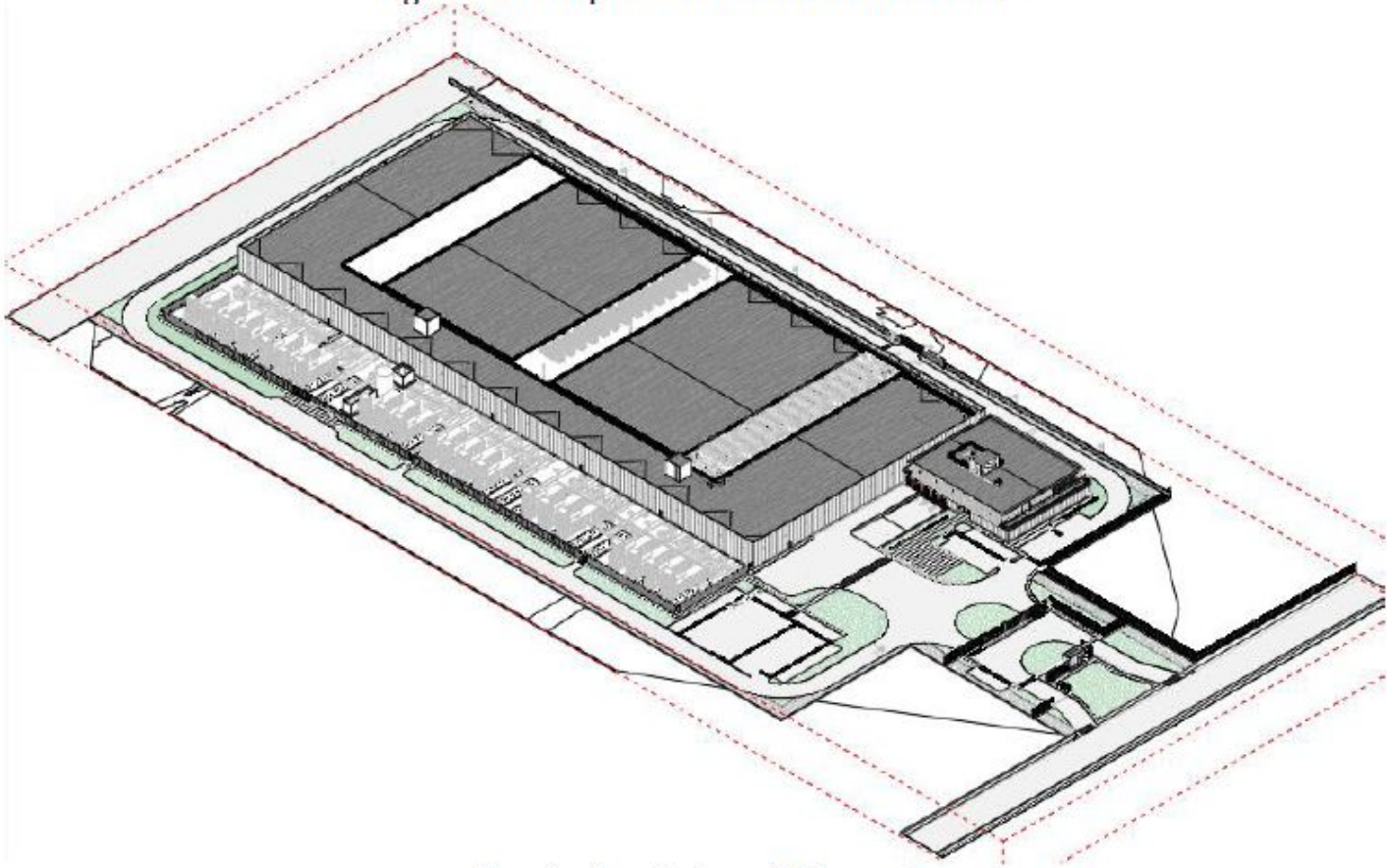

Fuente: Arquitectura del Proyecto

Figura 1-20. Layout del edificio data center

Fuente: Elaboración propia, 2023

Figura 1-21. Elevaciones

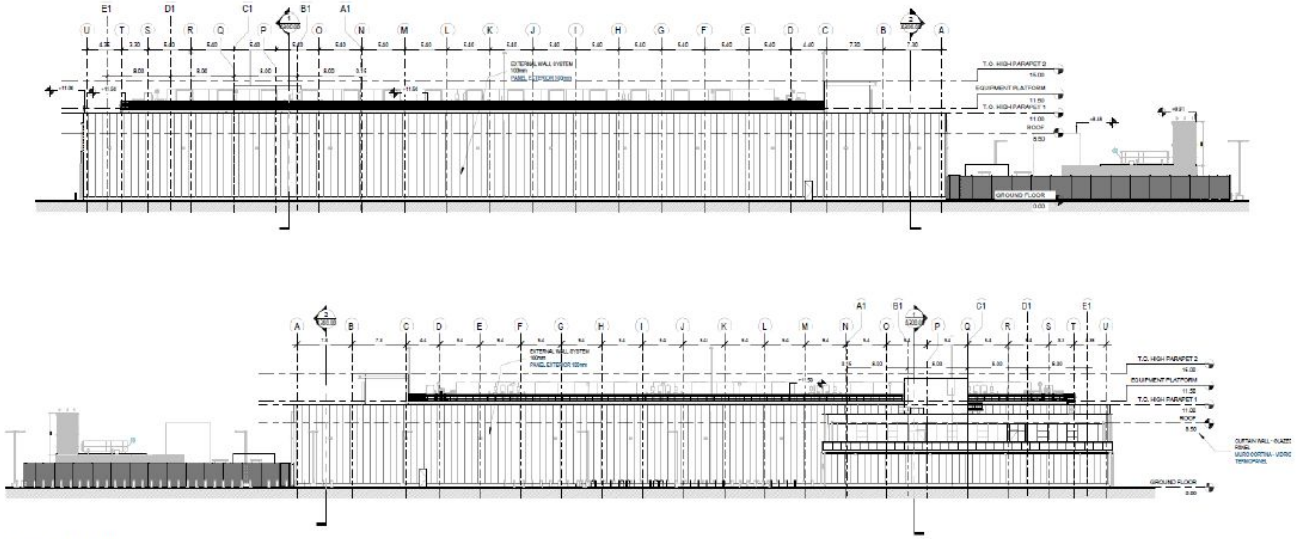

Fuente: Extracto plano "SCL04_ELEVACIONES", Anexo 1.3 de la DIA

Figura 1-22. Cortes

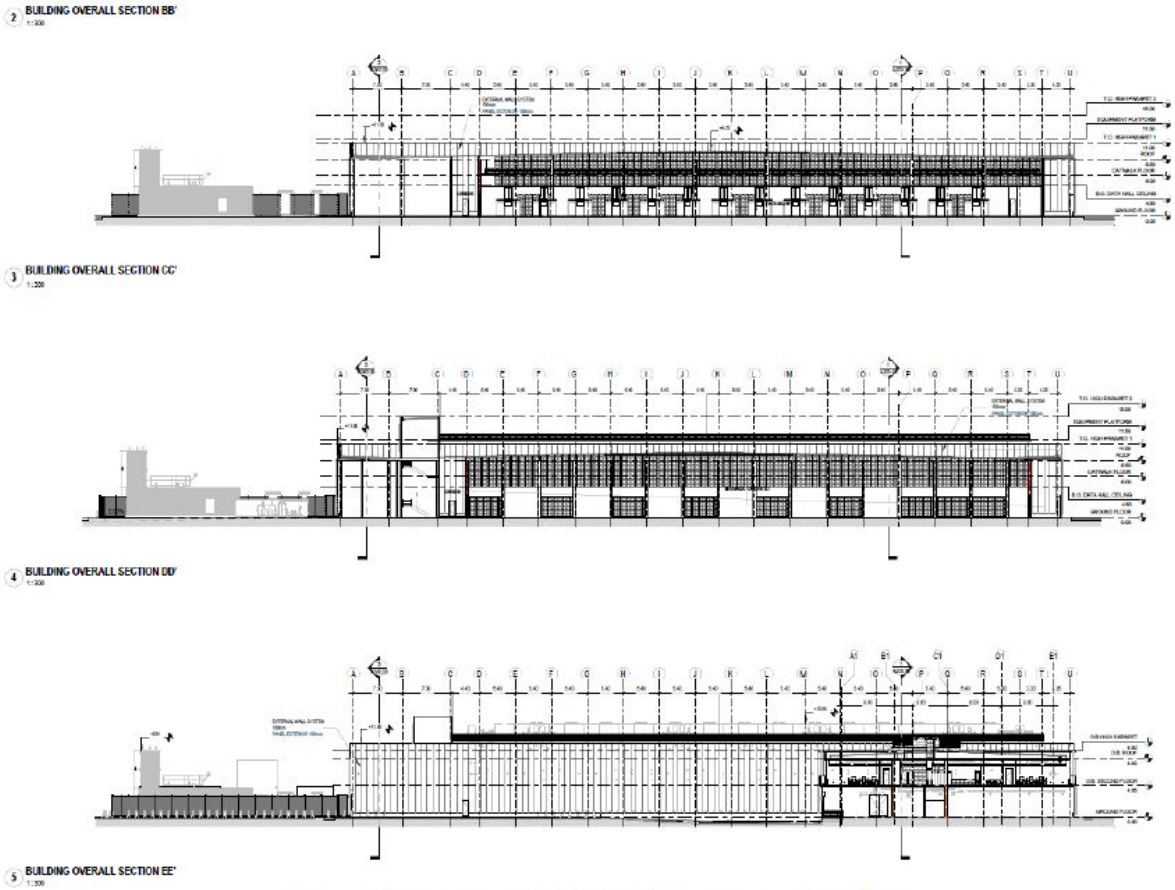

Fuente: Extracto plano "SCL04_CORTES", Anexo 1.3 de la DIA

Figura 1-23. Estacionamientos

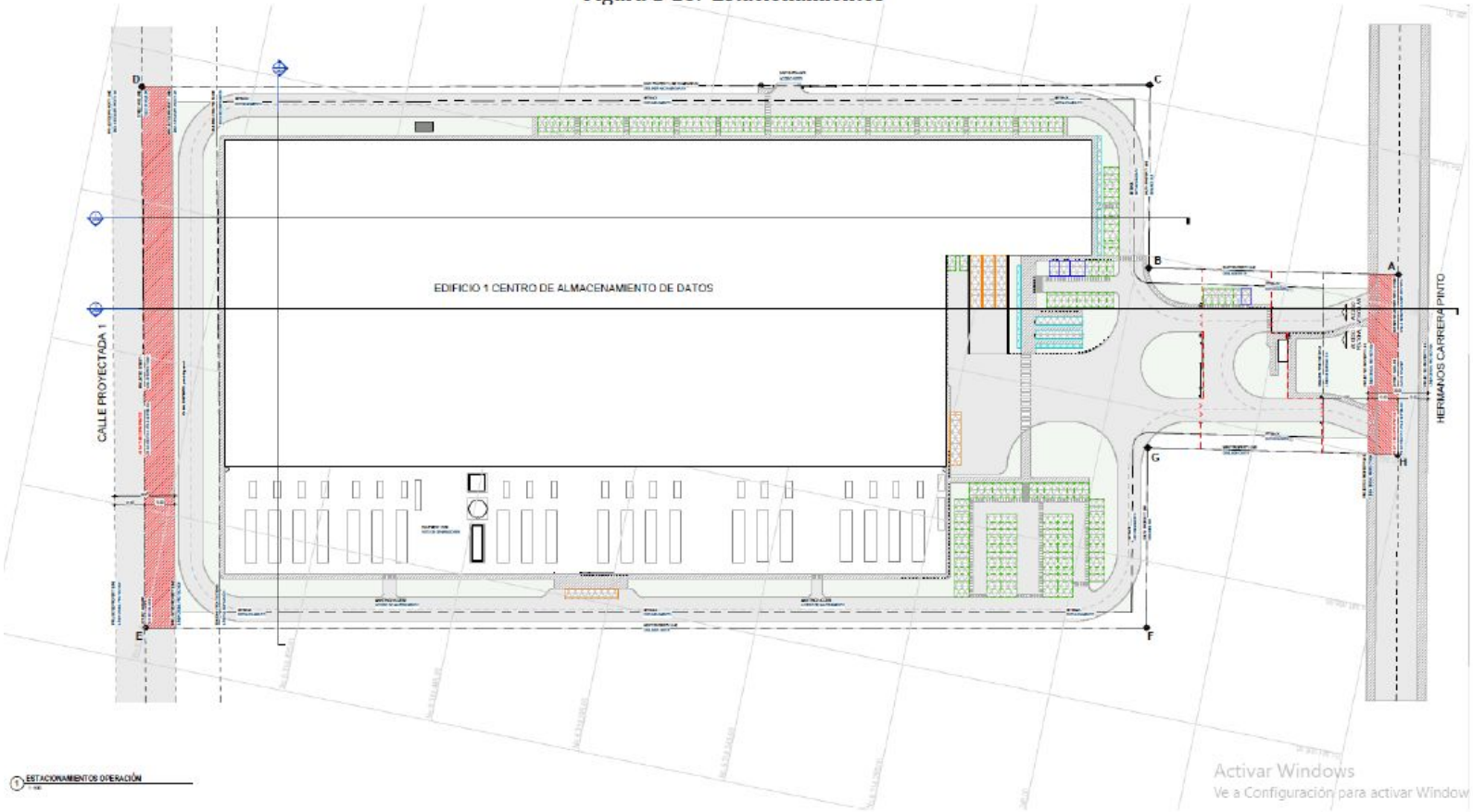

Fuente: Extracto plano "SCL04-D008-ESTACIONAMIENTOS OPERACIÓN", Anexo 1.3 de la DIA

Figura 1-36. Esquema de área primer piso

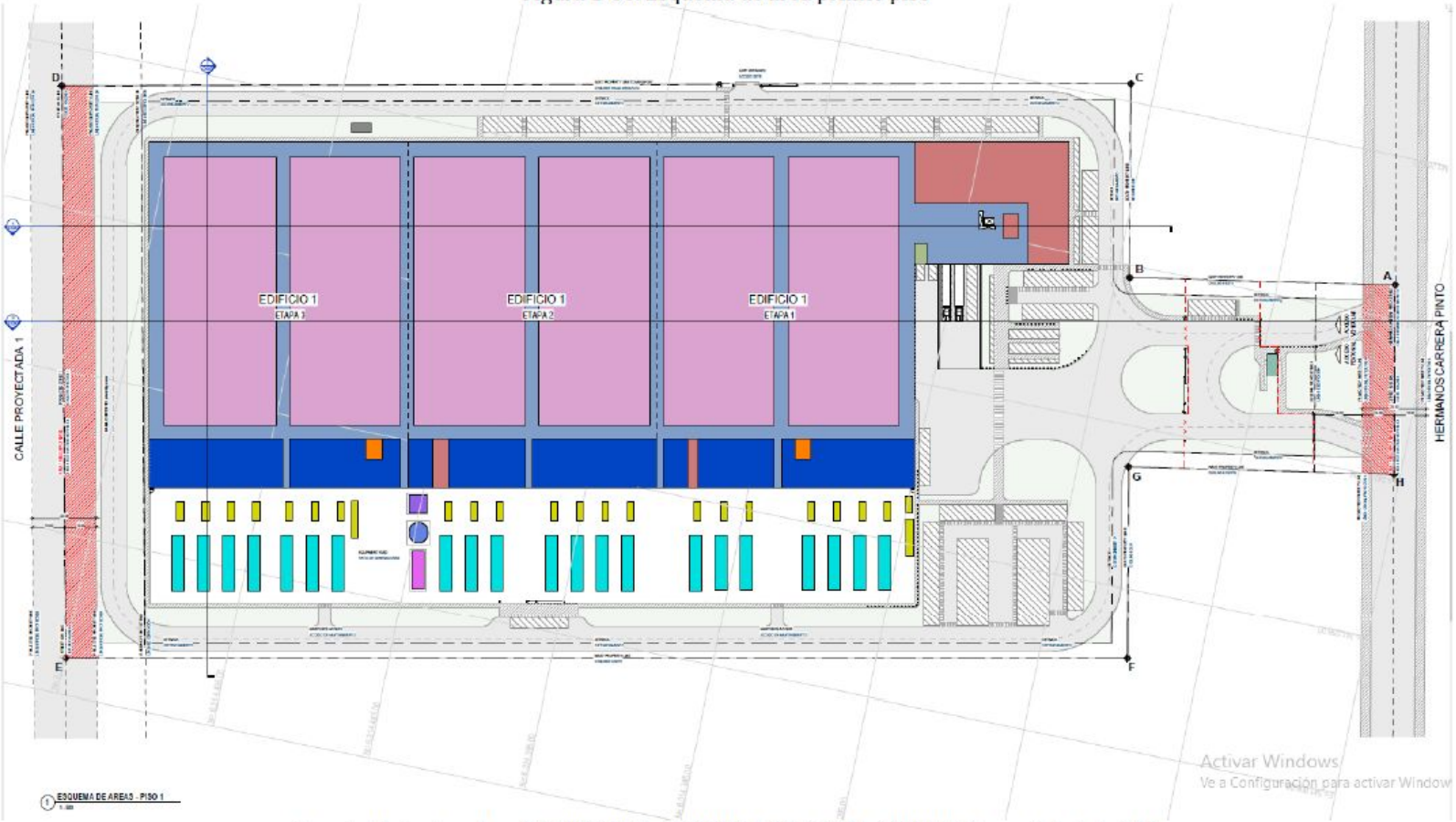

Fuente: Extracto plano "SCL04-D001-ESQUEMA DE AREAS - PISO 1", Anexo 1.3 de la DIA

Figura 1-37. Esquema de área segundo piso

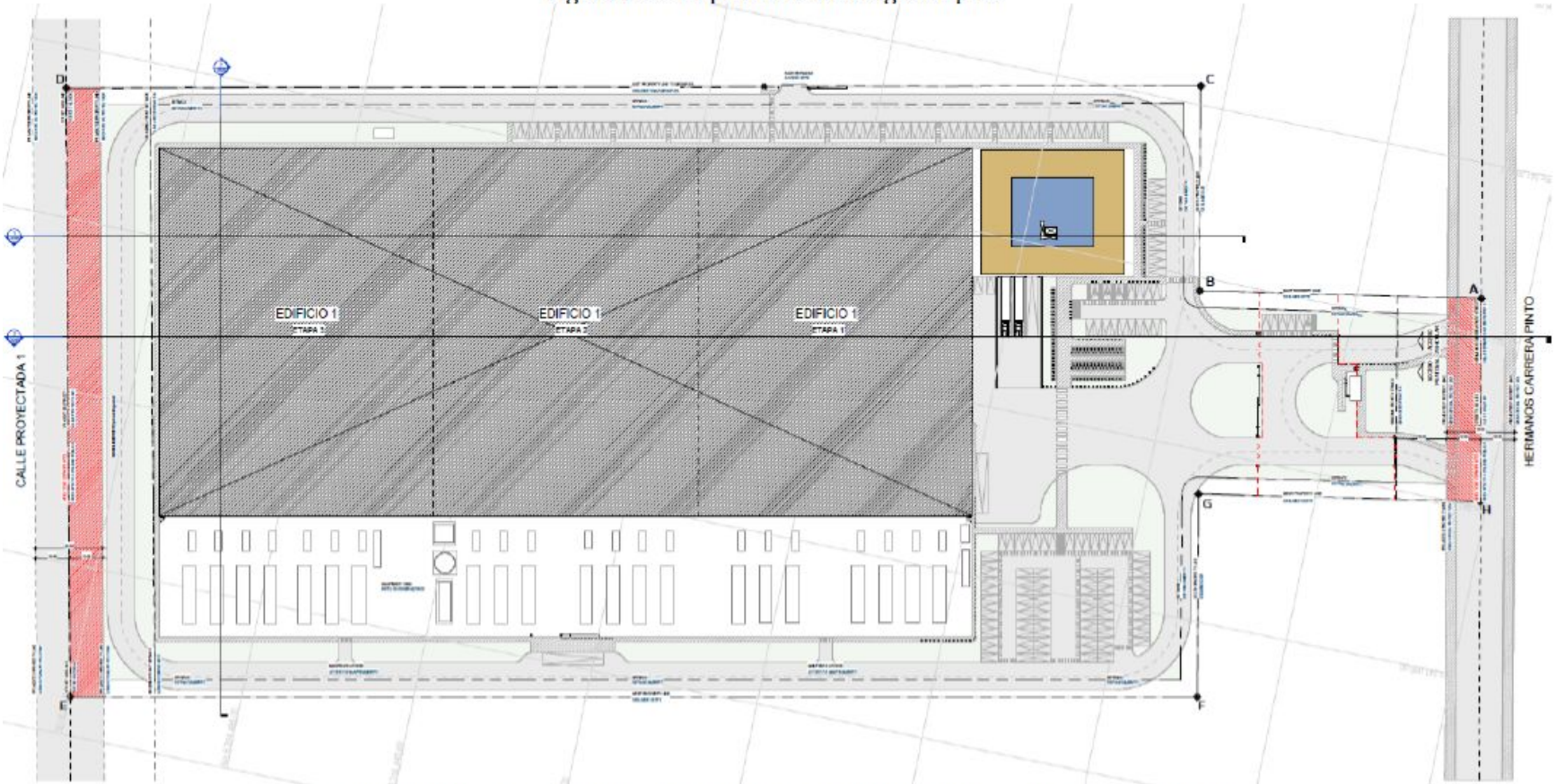

Fuente: Extracto plano "SCL04-D001-ESQUEMA DE AREAS - PISO 2", Anexo 1.3 de la DIA