SCALA Data Center Campus

Figura 1-1. Ubicación Proyecto – Nivel Regional

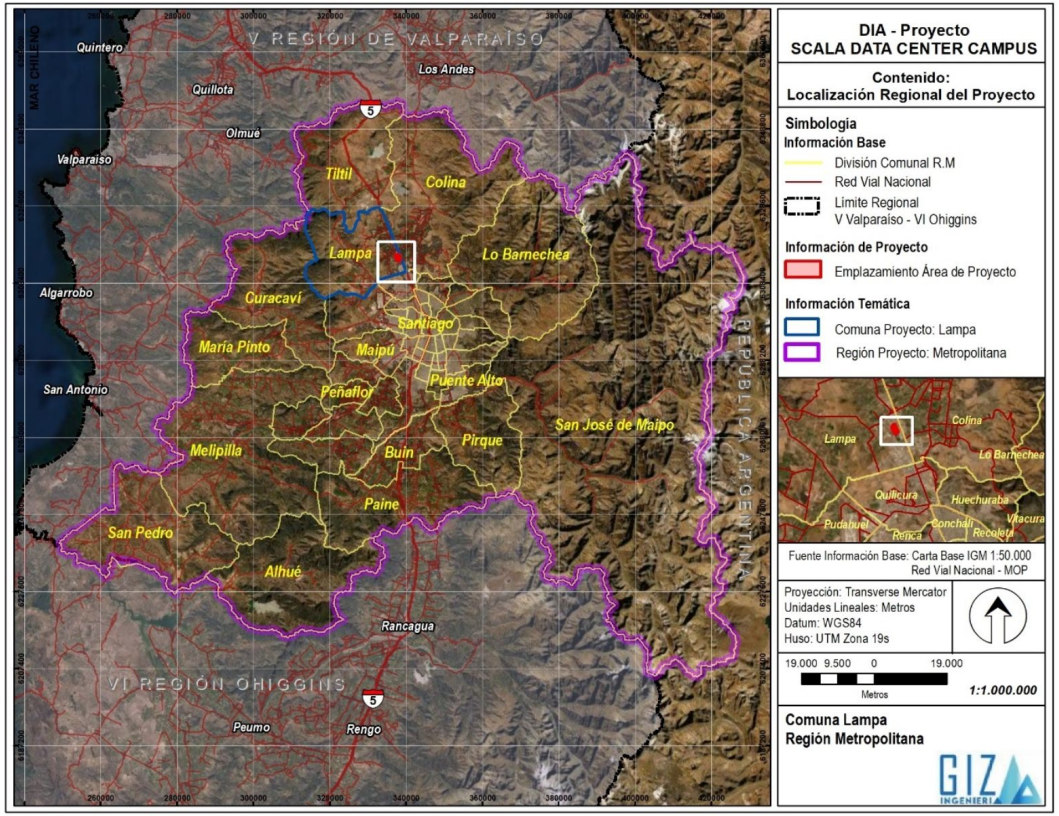

Fuente: Elaboración propia, 2021

Figura 1-2. Ubicación del Proyecto en Datum WGS84 – Nivel Comunal

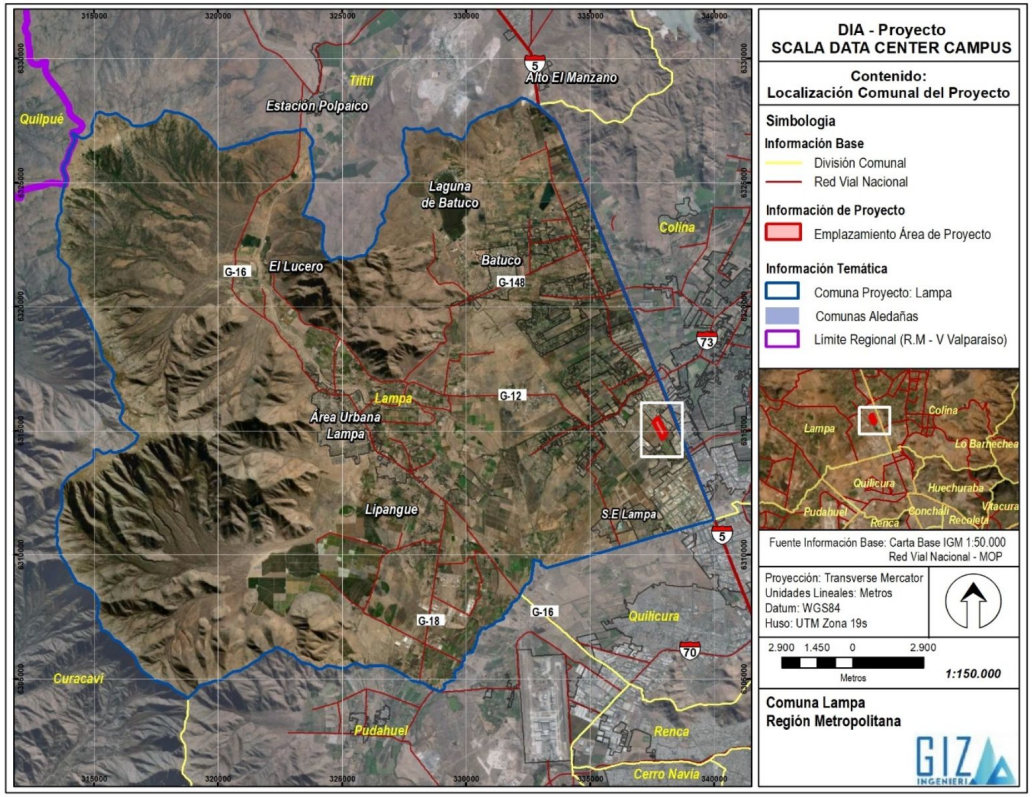

Fuente: Elaboración propia, 2021

Figura 1-13. Distribución de Edificios 1 y 2 (Etapa 1), y Edificio 3, Etapa 2

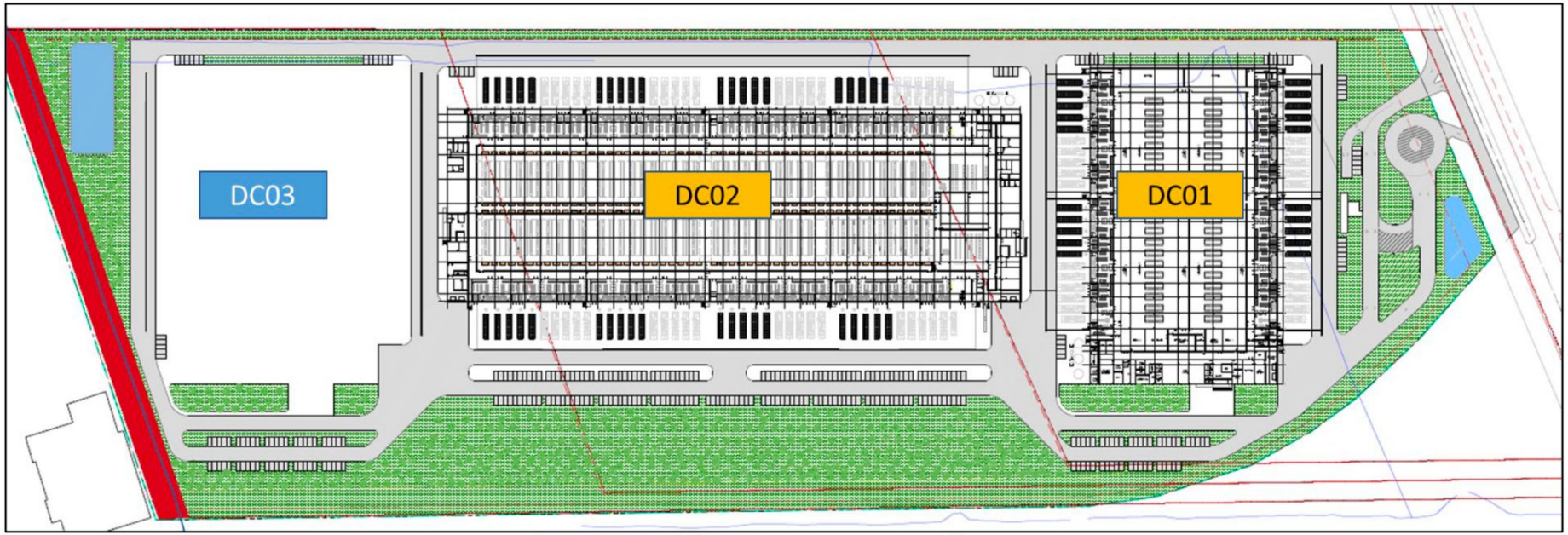

Fuente: Planos de arquitectura, Anexo 1.2 de la DIA

Figura 1-17. Red hidrográfica cercana al Proyecto

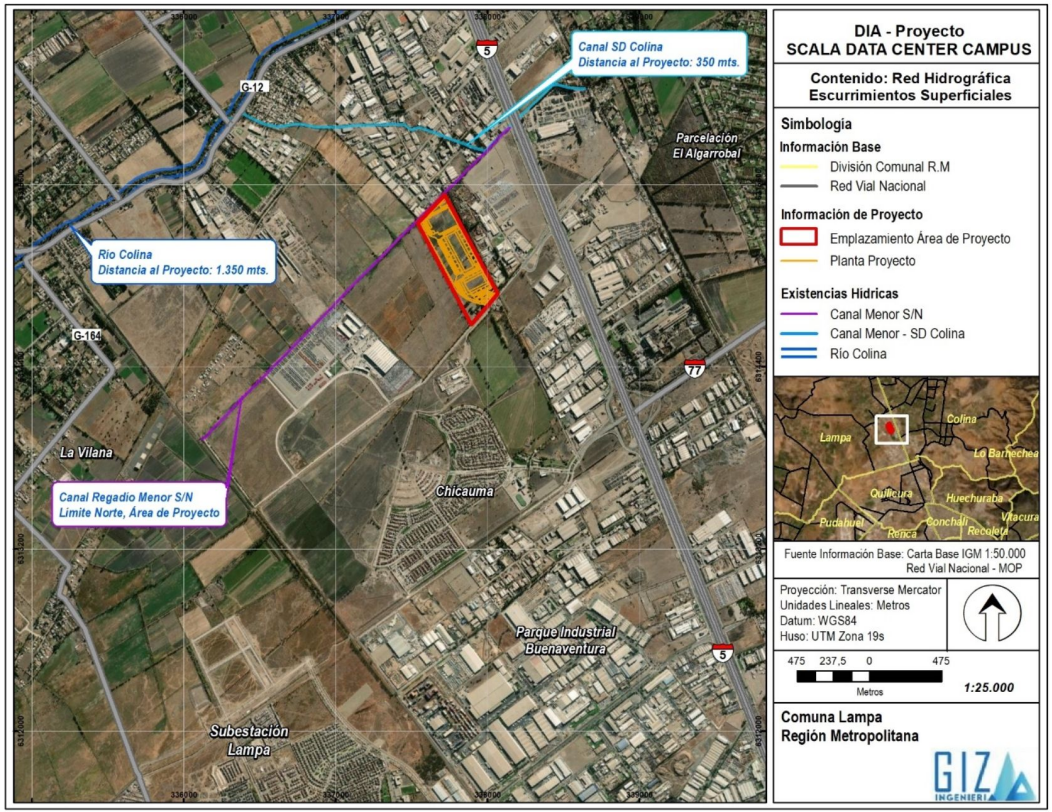

Fuente: Elaboración propia, 2021.

Figura 1-19. Punto del pozo de aguas subterráneas

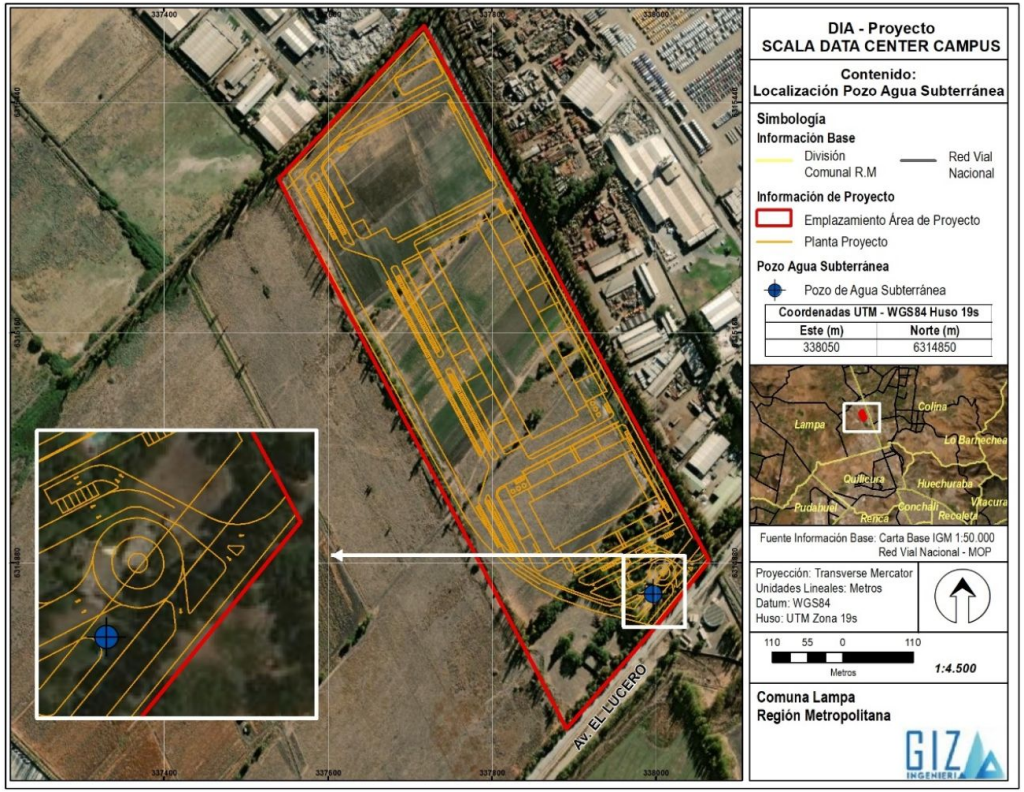

Fuente: Elaboración propia, 2021