Data Center III Entel -Pudahuel

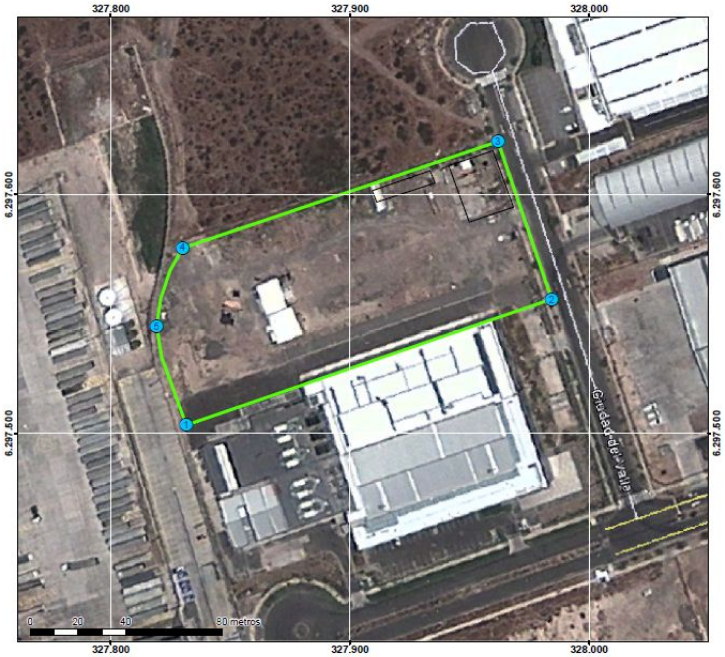

Leyenda

- Vértices Proyecto
- Límite Proyecto
- Edificación

Vértces	Coordenadas	
	Este	Norte
1	327.832	6.297.504
2	327.984	6.297.556
3	327.962	6.297.622
4	327.830	6.297.578
5	327.819	6.297.545

Datum WGS 84 Huso 19 Sur

DIA DATA CENTER ENTEL PUDAHUEL

FIGURA II-1

PLANO DE LOCALIZACIÓN

Escala 1:1.500

Fuente:
Imagen Google Earth.
Coordenadas:
WGS84 HUSO 19 sur.

Andalué Ambiental S.A.

FIGURA I-4: PERFIL LONGITUDINAL MÓDULO A Y B

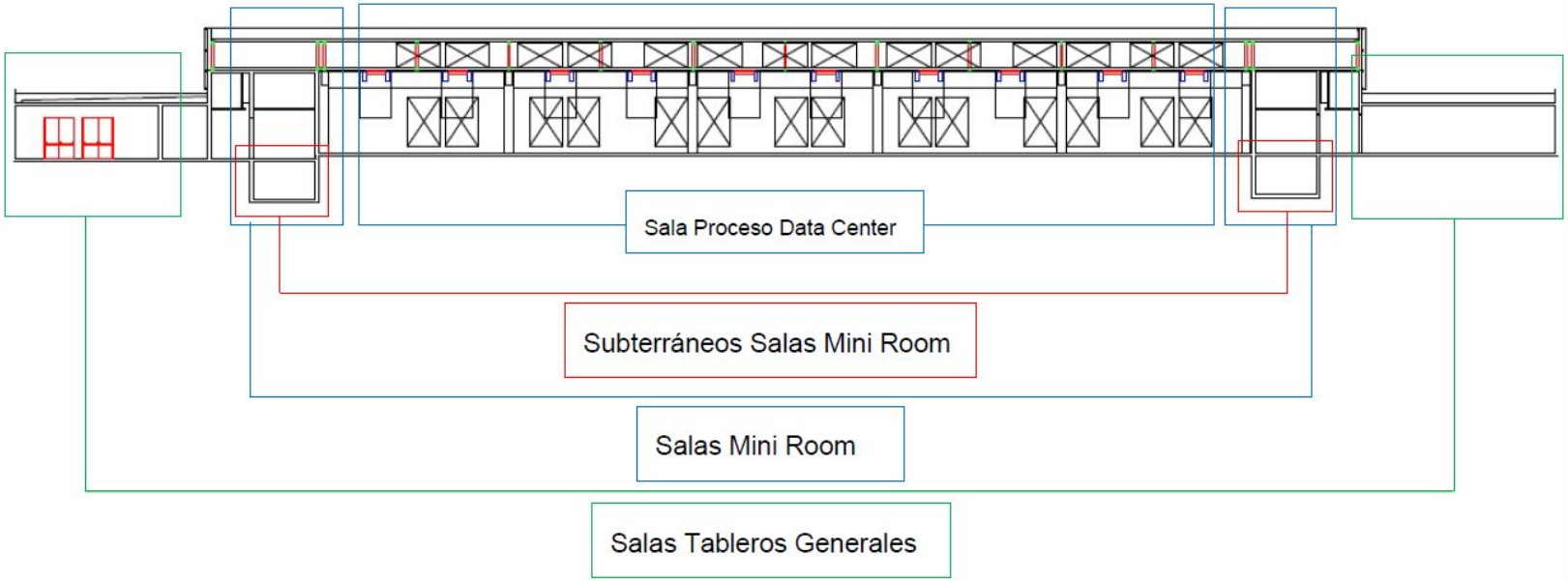
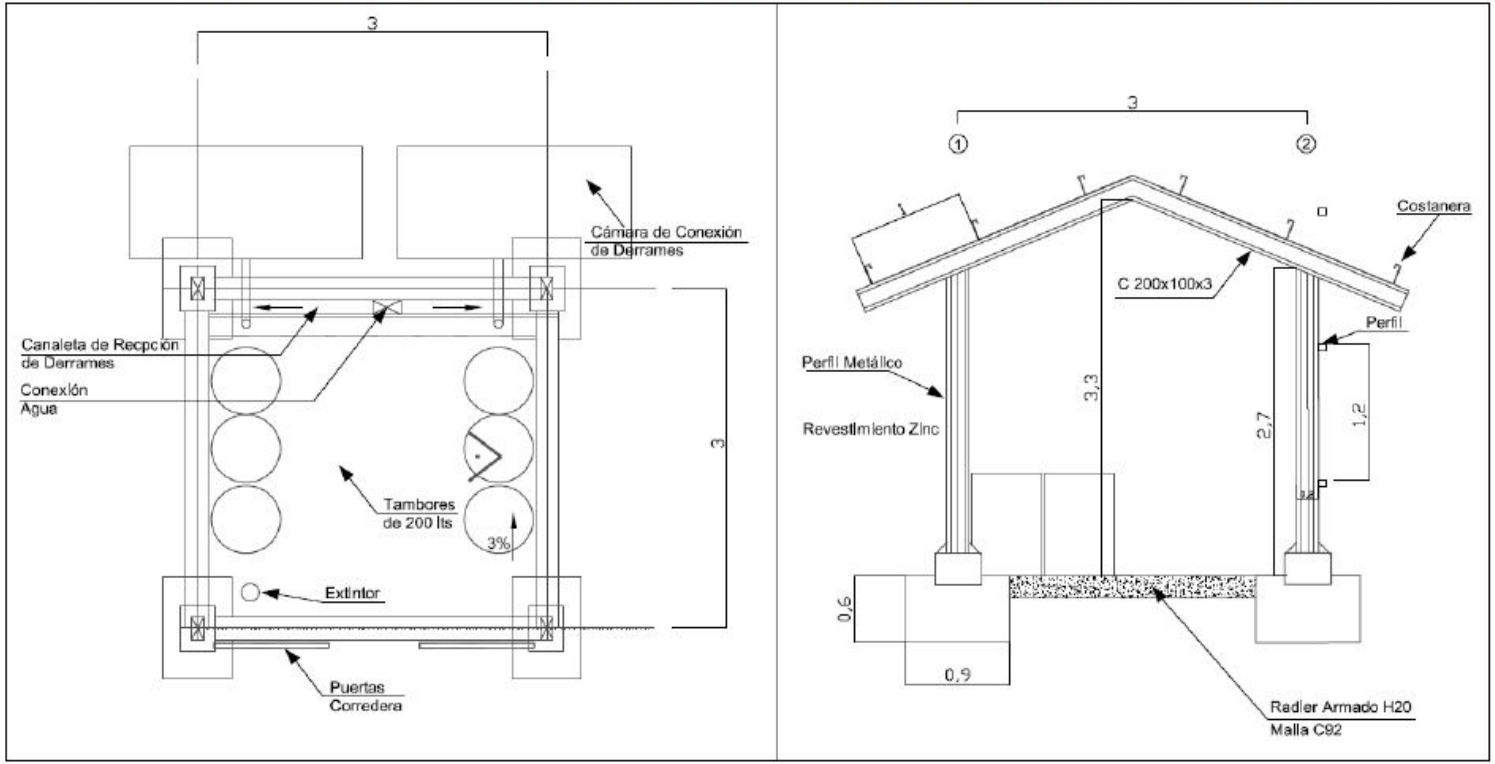
FIGURA III-2: BODEGA REFERENCIAL DE ALMACENAMIENTO TEMPORAL DE RESPEL