Data Center Ascenty

Figura 2. Identificación Data Center

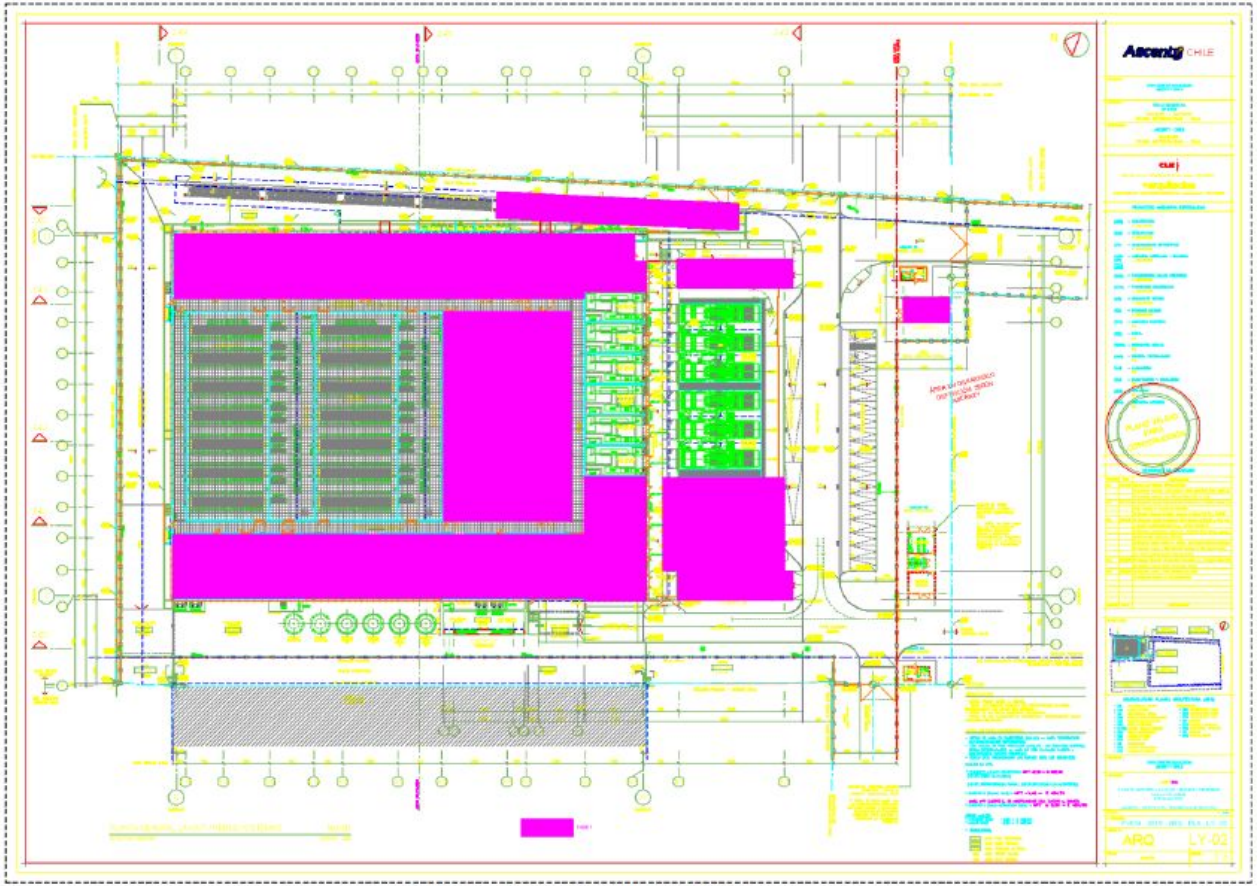

Fuente: Información proporcionada por el mandante.

Figura 3. Identificación del Proyecto y la Etapa Futura

Fuente: Información proporcionada por el mandante.

Figura 4. Localización del Proyecto a nivel regional y comunal

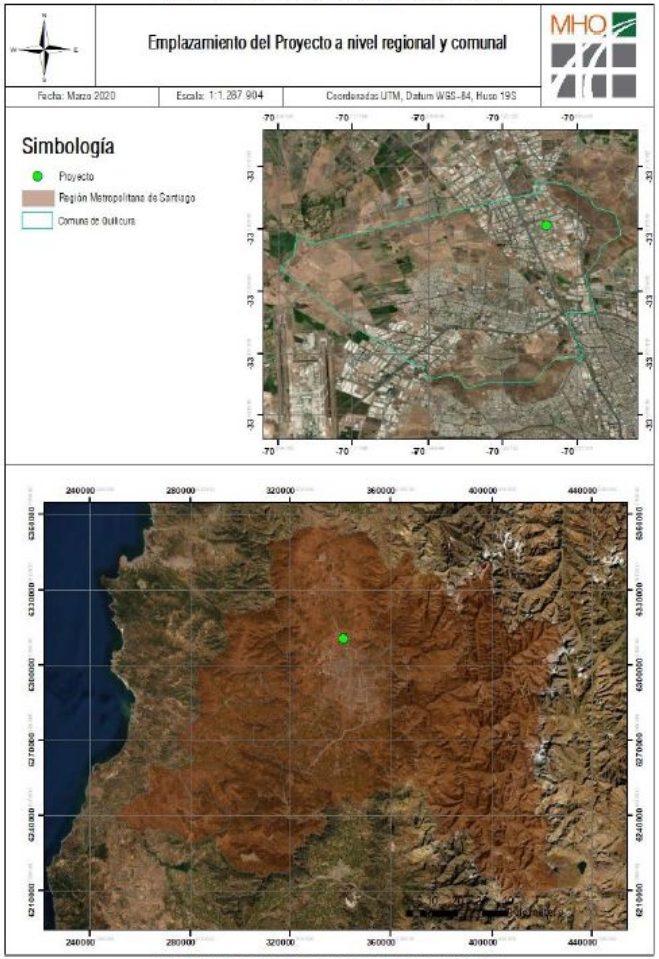

Fuente: Elaboración propia en base a los antecedentes el Proyecto

Figura 5. Emplazamiento del Proyecto



Fuente: Elaboración propia en base a los antecedentes el Proyecto

Figura 15. Partes y obras del Proyecto

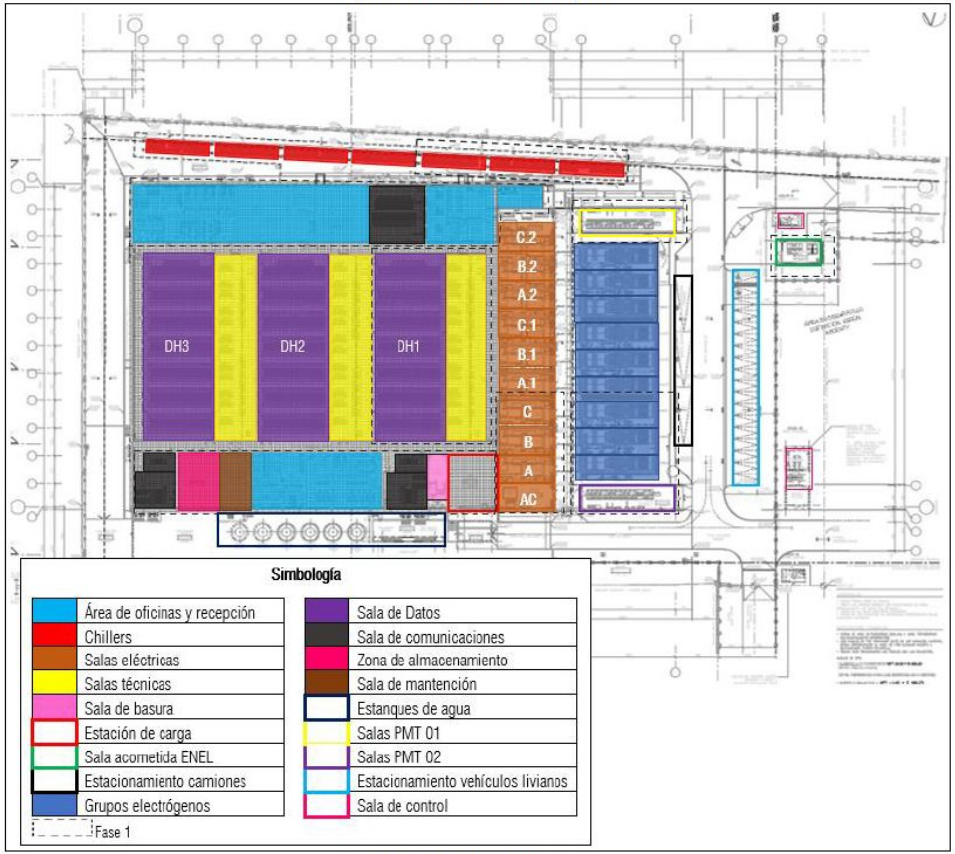

Fuente: Elaboración propia.

Figura 16. Elevación Norte

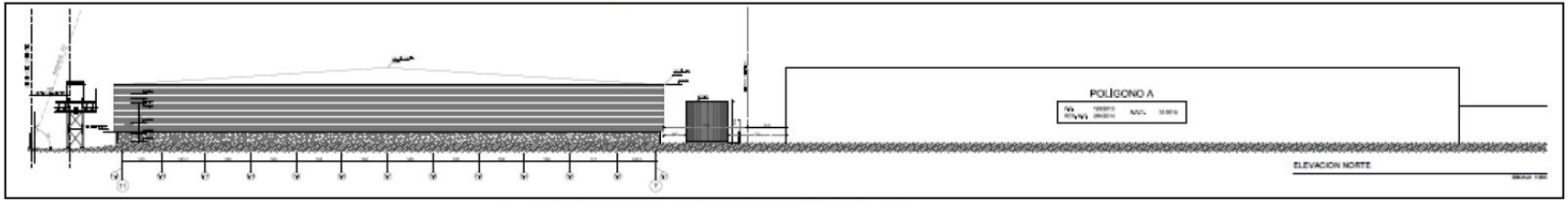

Fuente: Plano Elevaciones Cortes, Anexo 03. Planimetría

Figura 17: Elevación Sur

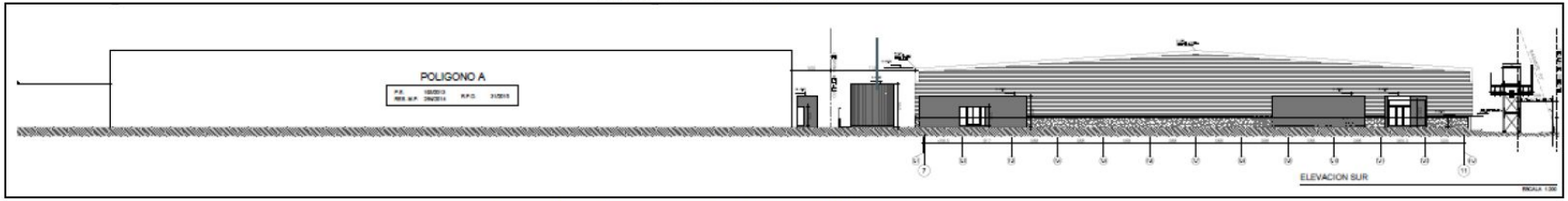

Fuente: Plano Elevaciones Cortes, Anexo 03. Planimetría

Figura 18. Elevación Oriente

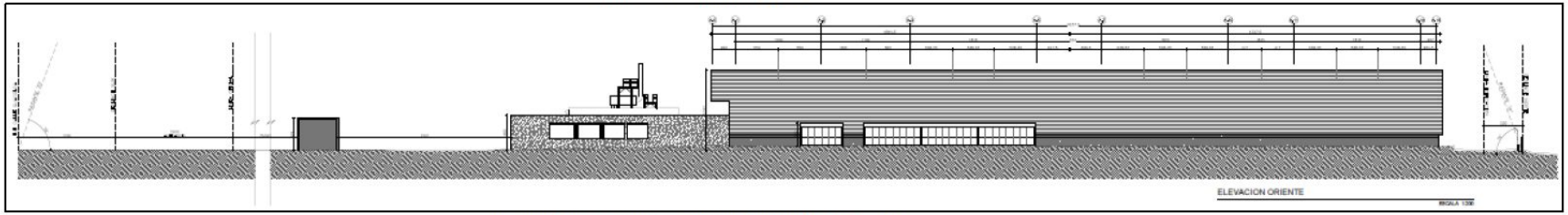

Fuente: Plano Elevaciones Cortes, Anexo 03. Planimetría

Figura 19. Elevación Poniente

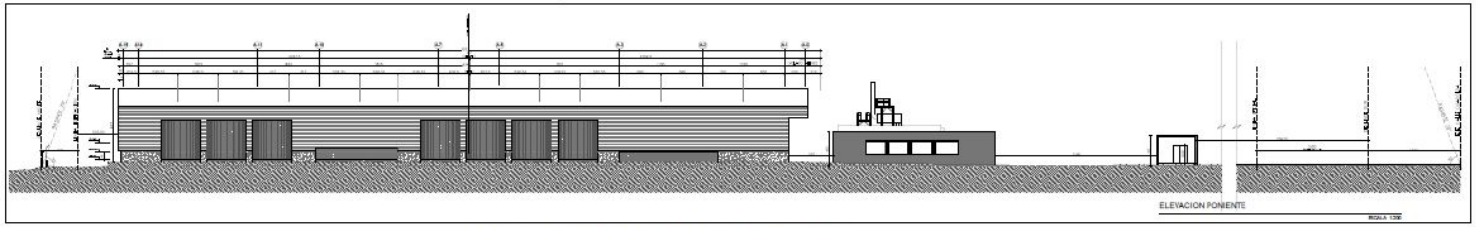

Fuente: Plano Elevaciones Cortes, Anexo 03. Planimetría

Figura 20. Corte Longitudinal

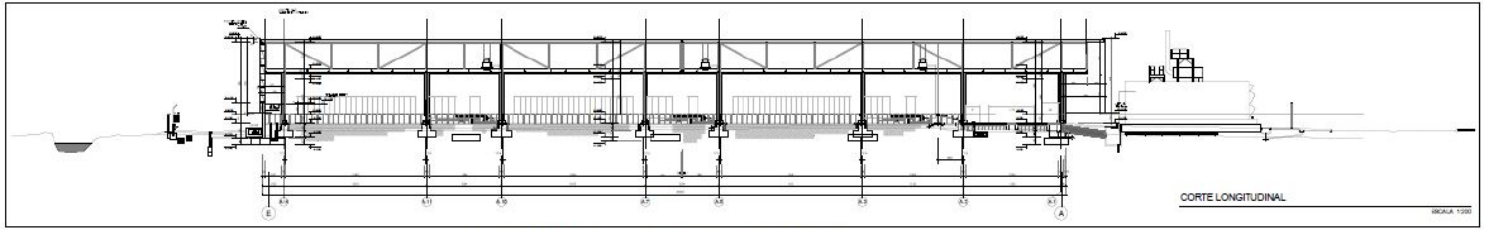

Fuente: Plano Elevaciones Cortes, Anexo 03. Planimetría

Figura 21. Corte Transversal

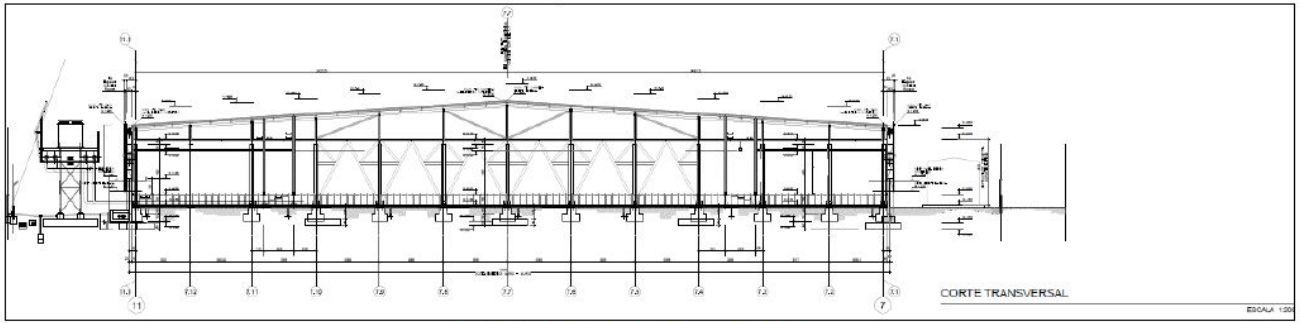

Fuente: Plano Elevaciones Cortes, Anexo 03. Planimetría