Data Center Chile 2

Figura 1-1. Etapas 1 y 2 del proyecto “Data Center Ascenty” y etapa 3 del nuevo Proyecto “Data Center Chile 2”.

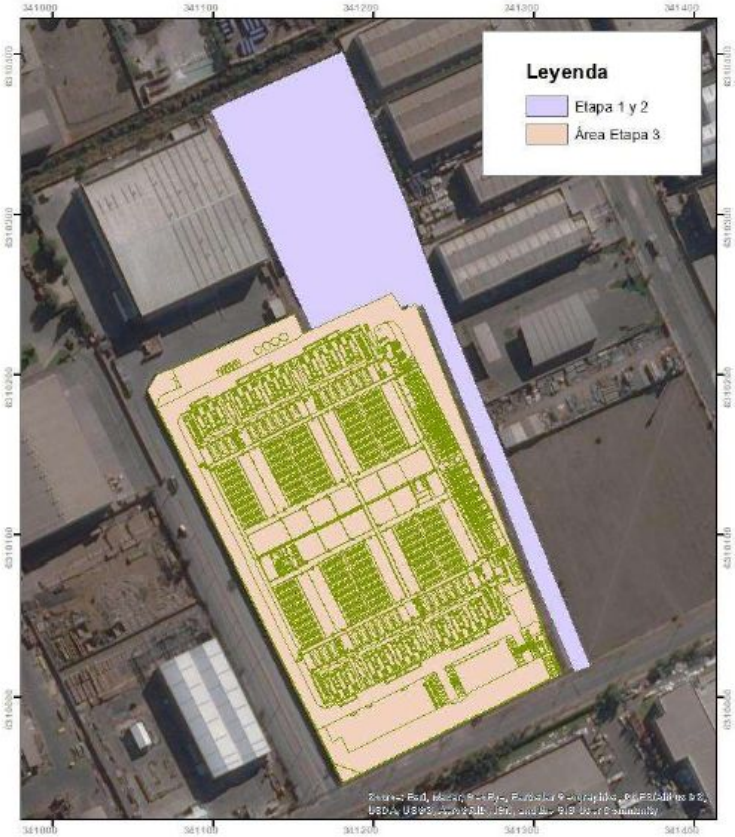

Fuente: Elaboración propia, 2021

Figura 1-2. Ubicación del Proyecto en Datum WGS84

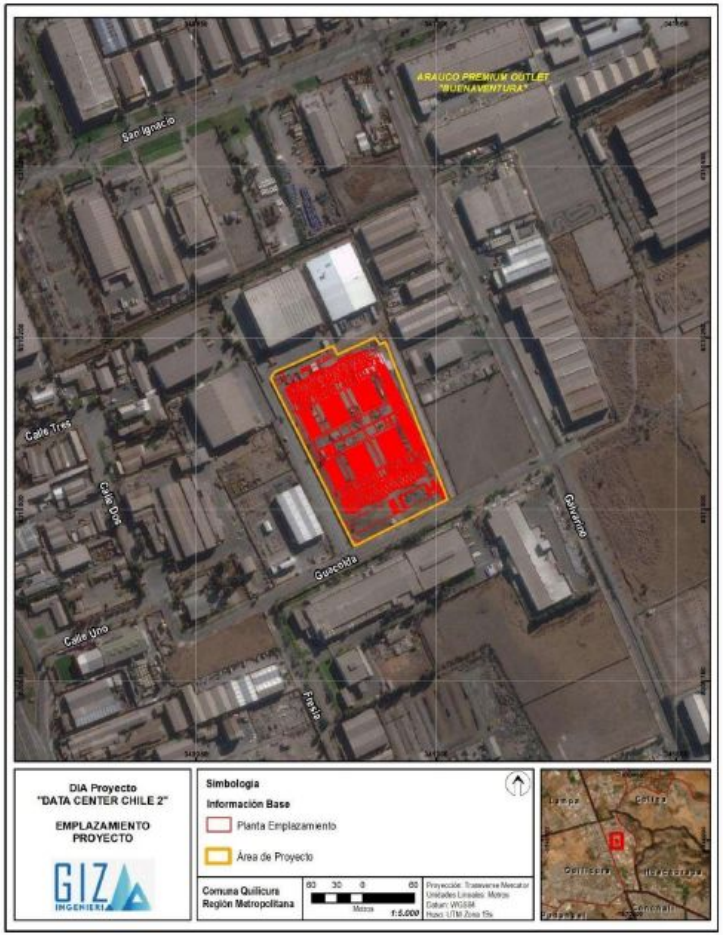

Fuente: Elaboración propia, 2021

Figura 1-3. Acceso al Proyecto.

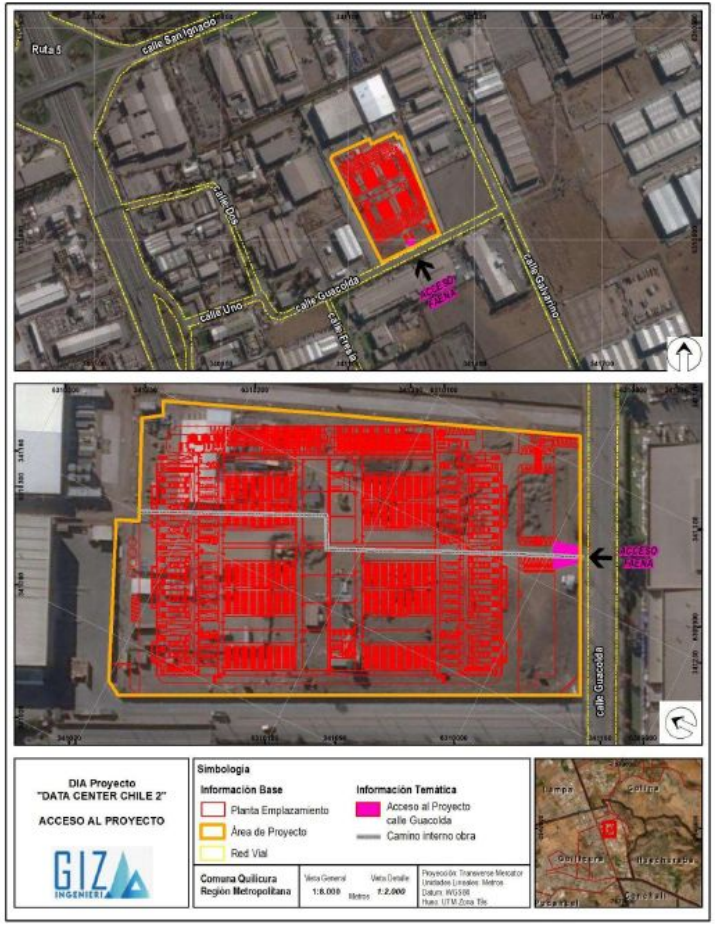

Fuente: Elaboración propia, 2021

Figura 1-11. Distribución de las partes y obras del Proyecto

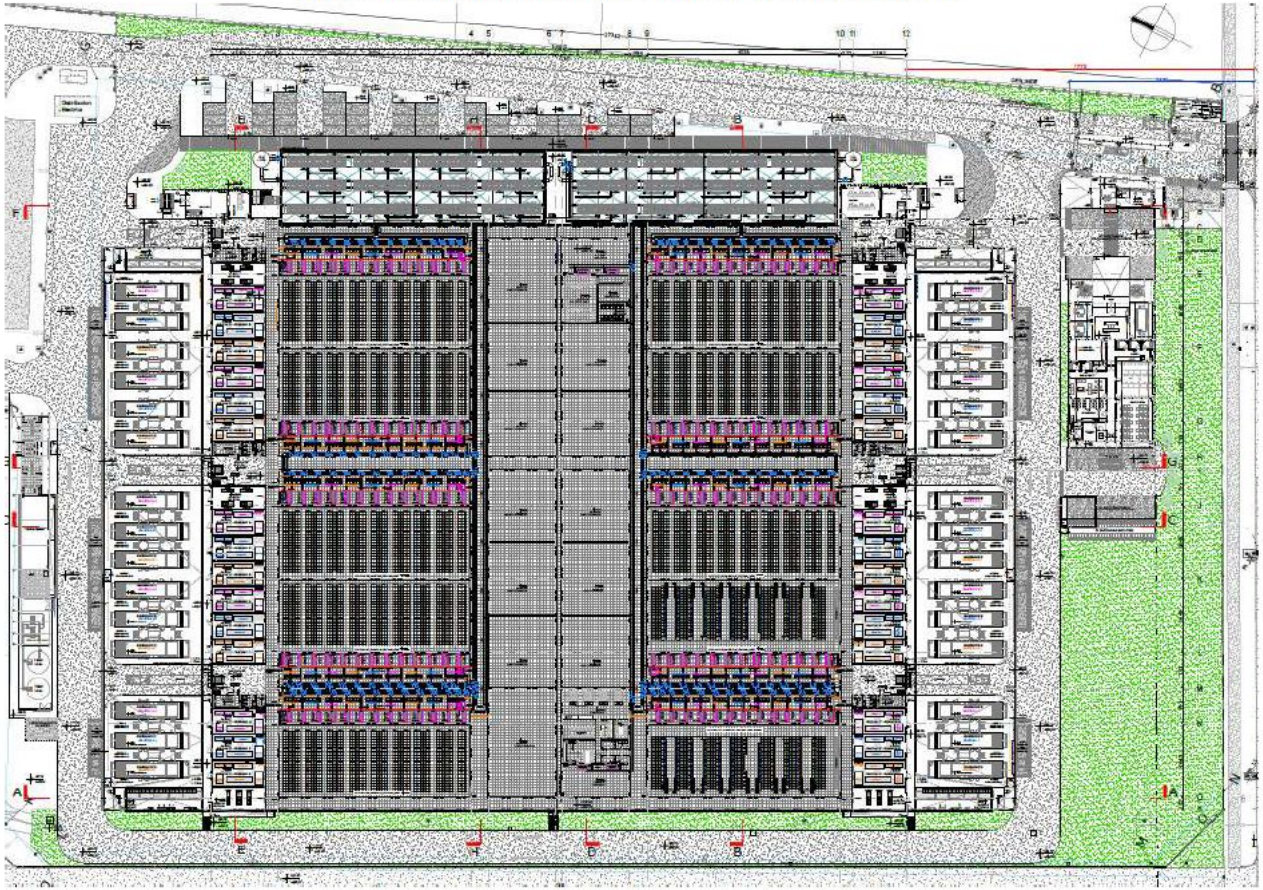

Fuente: Plano de arquitectura, Anexo 1.2 de la DIA

Figura 1-12. Elevación Norte y Sur del Proyecto.

Fuente: Plano de arquitectura, Anexo 1.2 de la DIA

Figura 1-13. Elevaciones vista poniente y oriente del Proyecto



Fuente: Plano de arquitectura, Anexo 1.2 de la DIA