Centro de Almacenamiento de Datos Puente Alto

FIGURA I-1: REPRESENTACIÓN CARTOGRÁFICA DEL PROYECTO

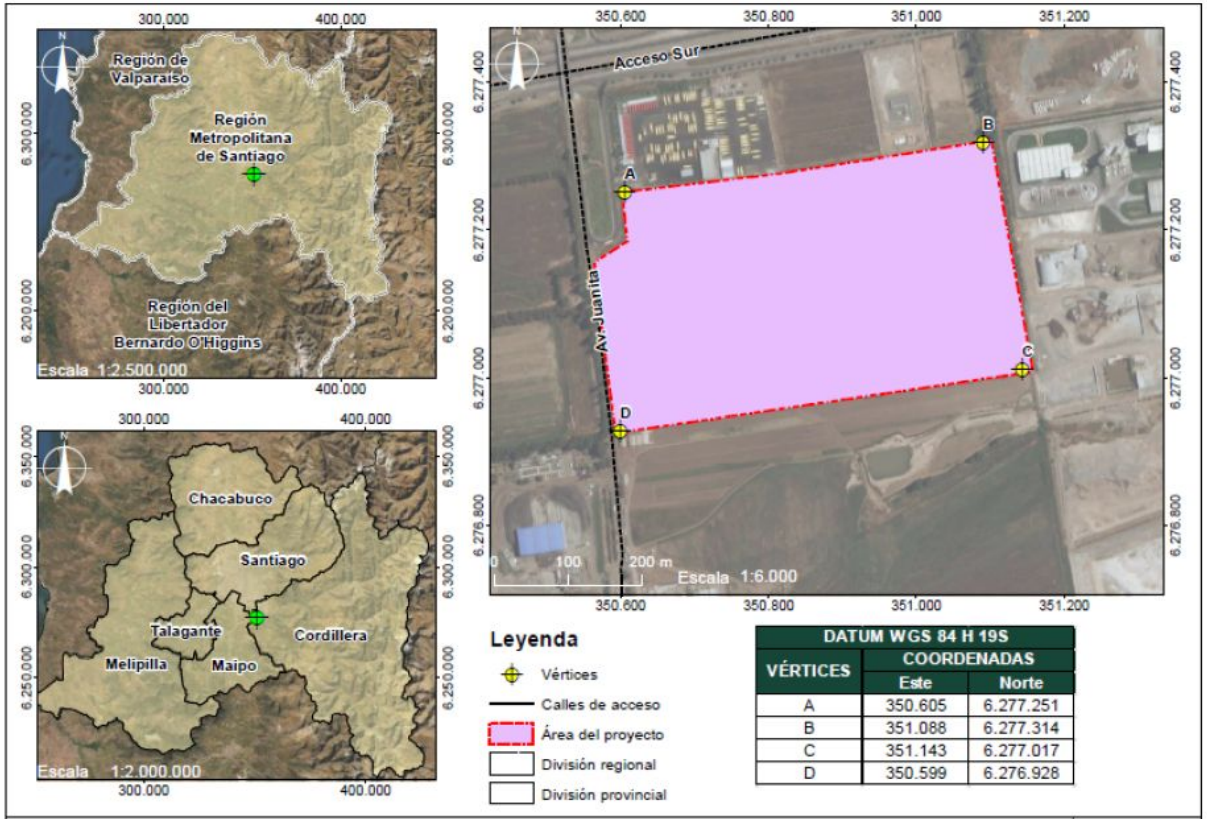

DATUM WGS 84 H 19S		
VÉRTICES	COORDENADAS	
	Este	Norte
A	350.605	6.277.251
B	351.088	6.277.314
C	351.143	6.277.017
D	350.599	6.276.928

PROYECTO EN CONTEXTO REGIONAL, PROVINCIAL Y LOCAL

CENTRO DE ALMACENAMIENTO DE DATOS PUENTE ALTO

Escala: Las Indicadas

ORBE CONSULTORES

Fuente: Elaboración Propia. Proyección cartográfica UTM Datum WGS84 H19S

FIGURA I-4: PARTES Y OBRAS PERMANENTES DEL PROYECTO

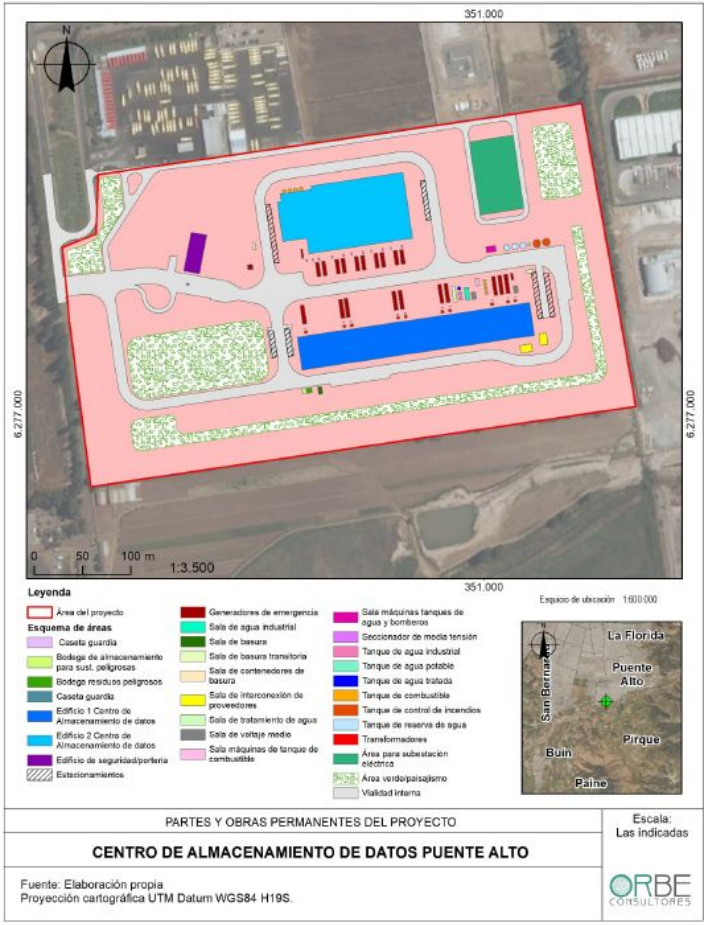

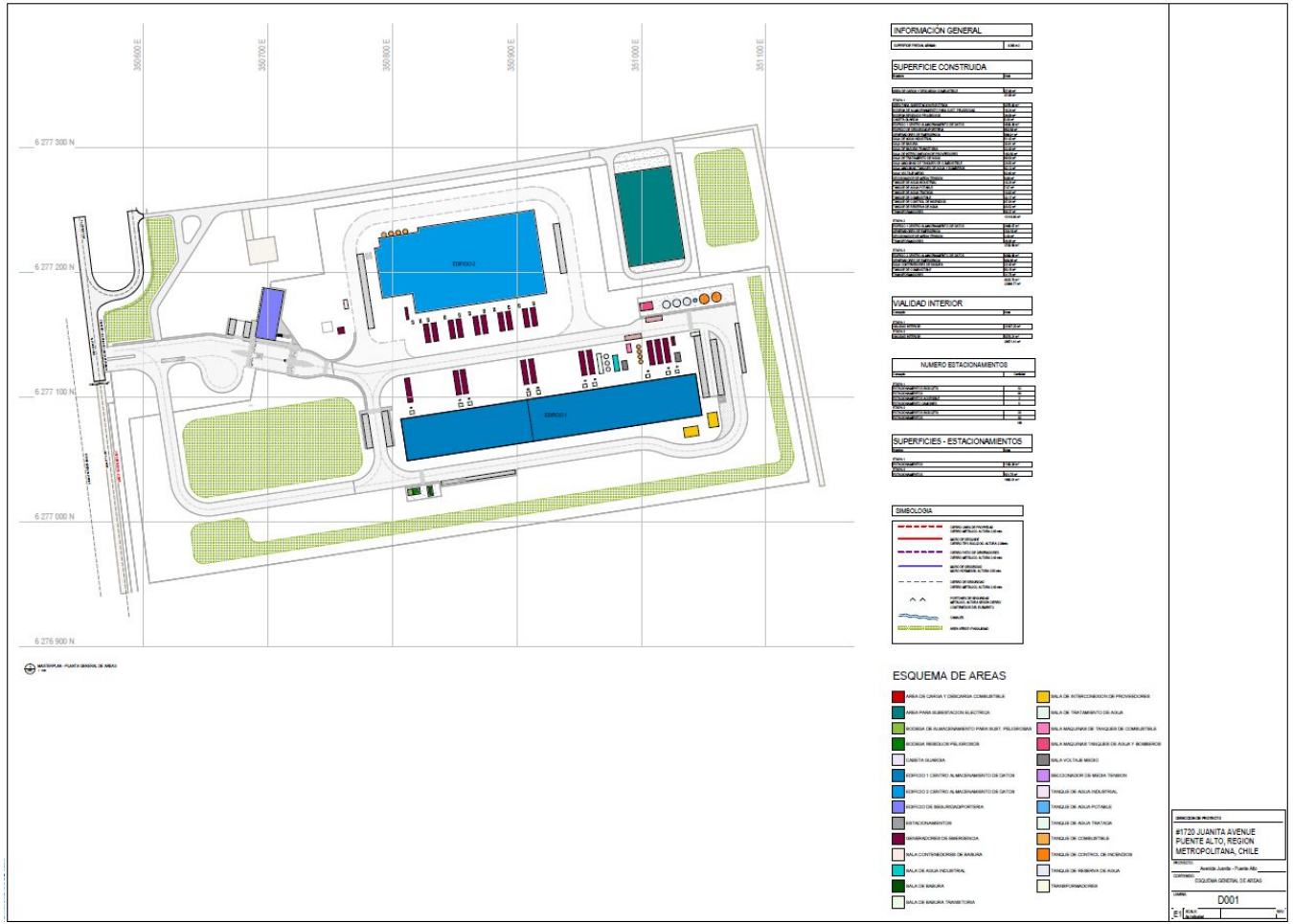
INFORMACIÓN GENERAL
SUPERFICIE CONSTRUIDA
VIALIDAD INTERIOR
NUMERO ESTACIONAMIENTOS
SUPERFICIES - ESTACIONAMIENTOS
SIMBOLOGIA
ESQUEMA DE AREAS
#1720 JUANITA AVENUE
PUENTE ALTO, REGION
METROPOLITANA, CHILE
ESQUEMA GENERAL DE AREAS
D001