Scala Data Center Curauma

Figura 1-4. Ubicación Etapa 4

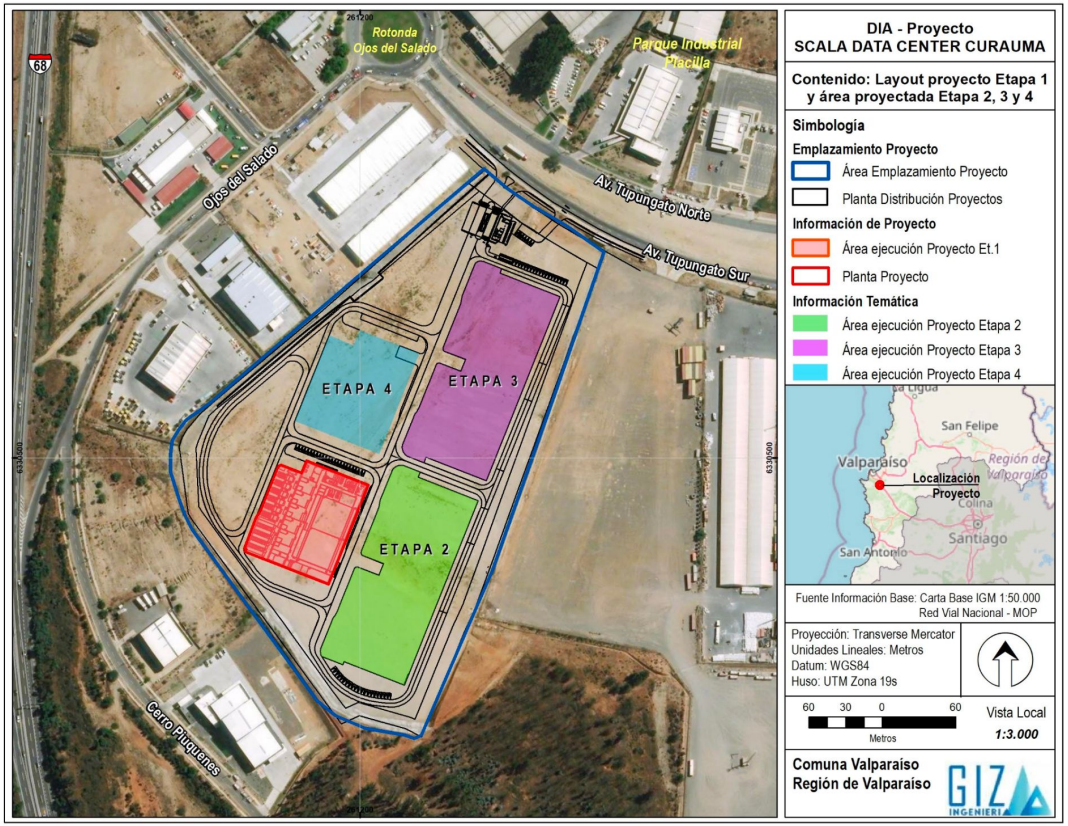

Fuente: Elaboración propia, 2022

Figura 1-5. Ubicación del Proyecto en Datum WGS84

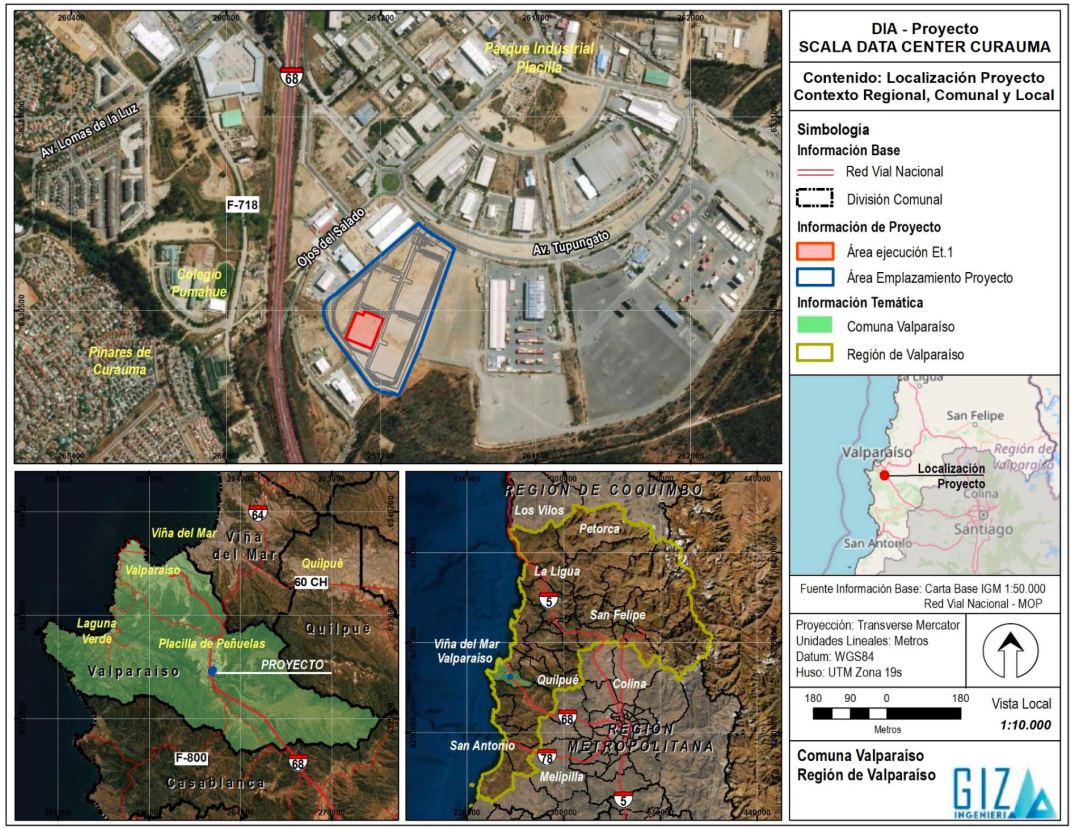

Fuente: Elaboración propia, 2022

Figura 1-17. Elevaciones

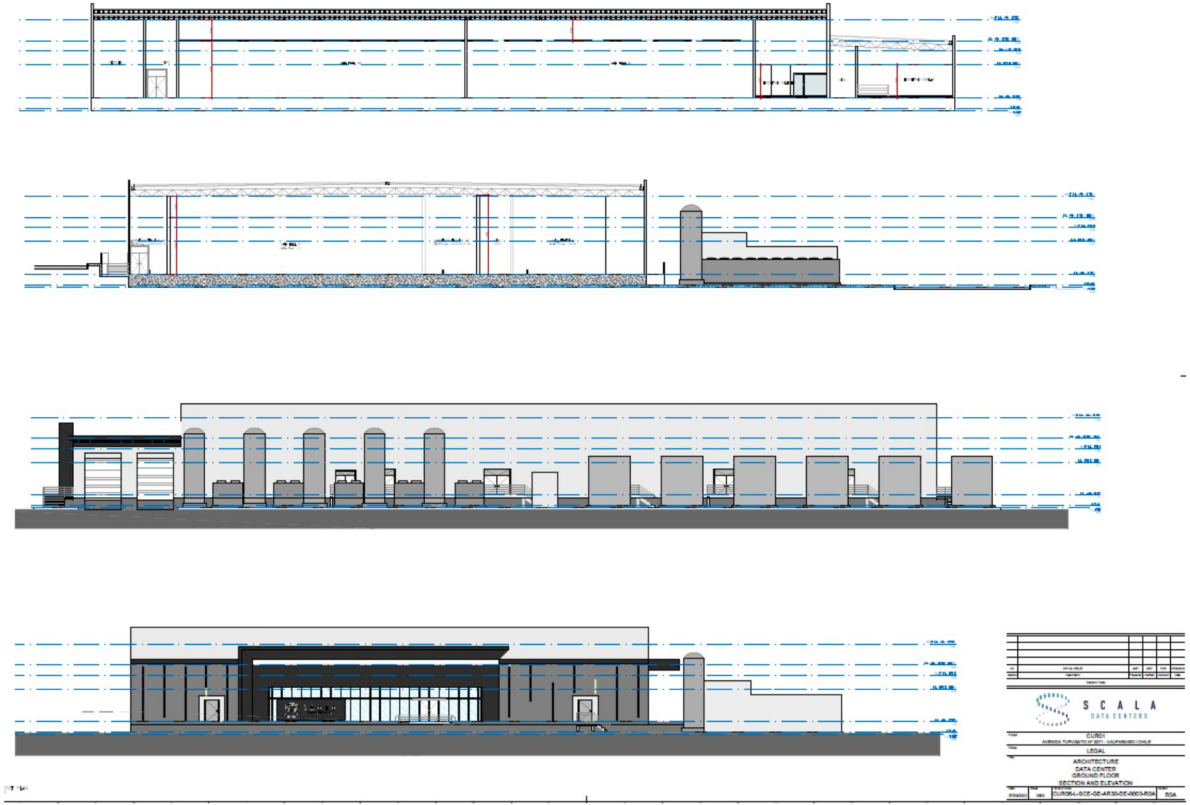

Fuente: Extracto plano “CUR06-L-SCE-DC02-AR30-DE-0003-R0A”, Anexo 1.3 de la DIA

Figura 1-18. Distribución de las partes y obras del data center

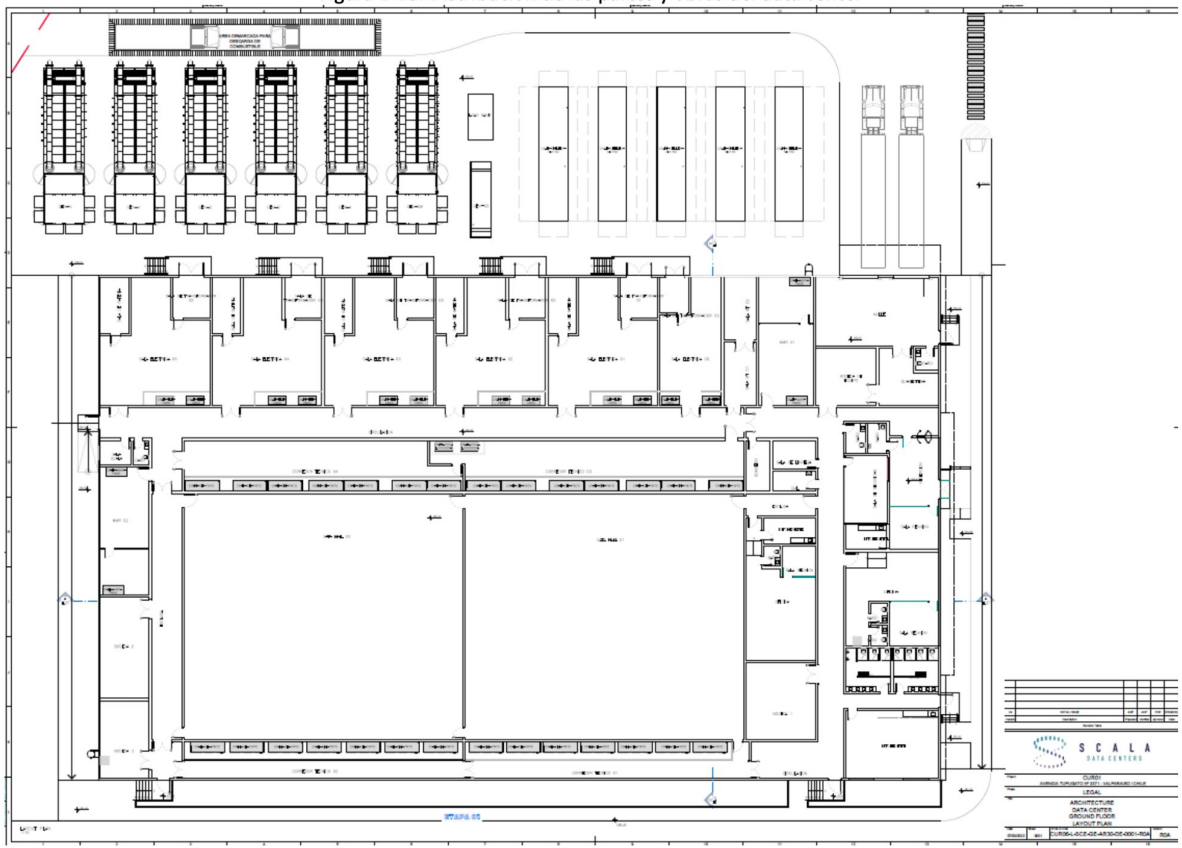

Fuente: Extracto Plano "CUR06-LAY-XREF-0LV- R01", Anexo 1.3 de la DIA

Figura 1-23. Grupo generador y estanque de combustible

Grupo generador Cat 3516E 3.437 KVA/2.750 kW

Bore – mm (in)	170 (6.69)
Stroke – mm (in)	215 (8.47)
Displacement – L (in³)	78.1 (4766)
Compression Ratio	14.7:1
Aspiration	TA
Fuel System	EUI
Governor Type	ADEM™ A5

Image shown may not reflect actual configuration

Standby 60 Hz ekW (kVA)	Mission Critical 60 Hz ekW (kVA)	Prime 60 Hz ekW (kVA)	Emissions Performance
2750 (3437)	2750 (3437)	2500 (3125)	U.S. EPA Certified for Emergency Stationary Applications (Tier 2)

Cabina grupo generador y estanque de combustible (Sub base)

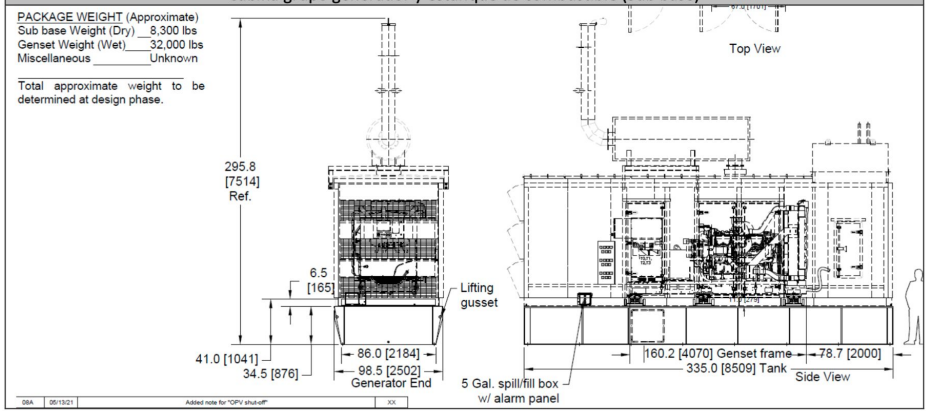

Fuente: Extracto Especificaciones técnicas, Anexo 1.2 de la DIA

Figura 1-28. Equipos Chillers Vertiv

Fuente: Información aportada por el titular, 2022

Figura 1-29. Modelos equipos CRAH

VERTI PW large	VERTI PW medium

Fuente: Extracto Especificaciones técnicas, Anexo 1.2 de la DIA

Ubicación del Proyecto en el Mapa Geológico del área de Valparaíso – Curacaví

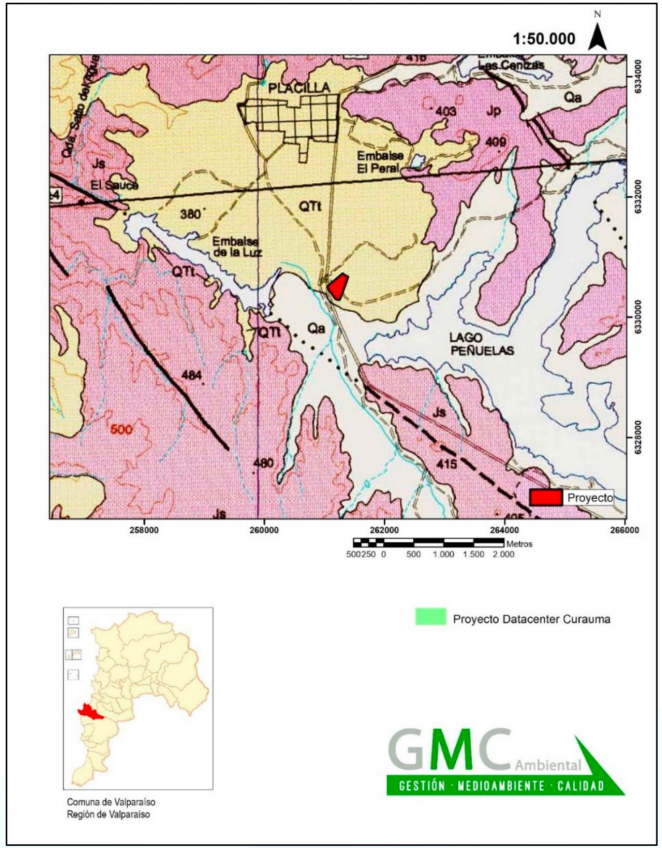

Fuente: Extracto Informe de caracterización geológica e hidrogeológica, Anexo 3.5 de la DIA

Figura 3-7. Red hidrográfica en el área de influencia del Proyecto

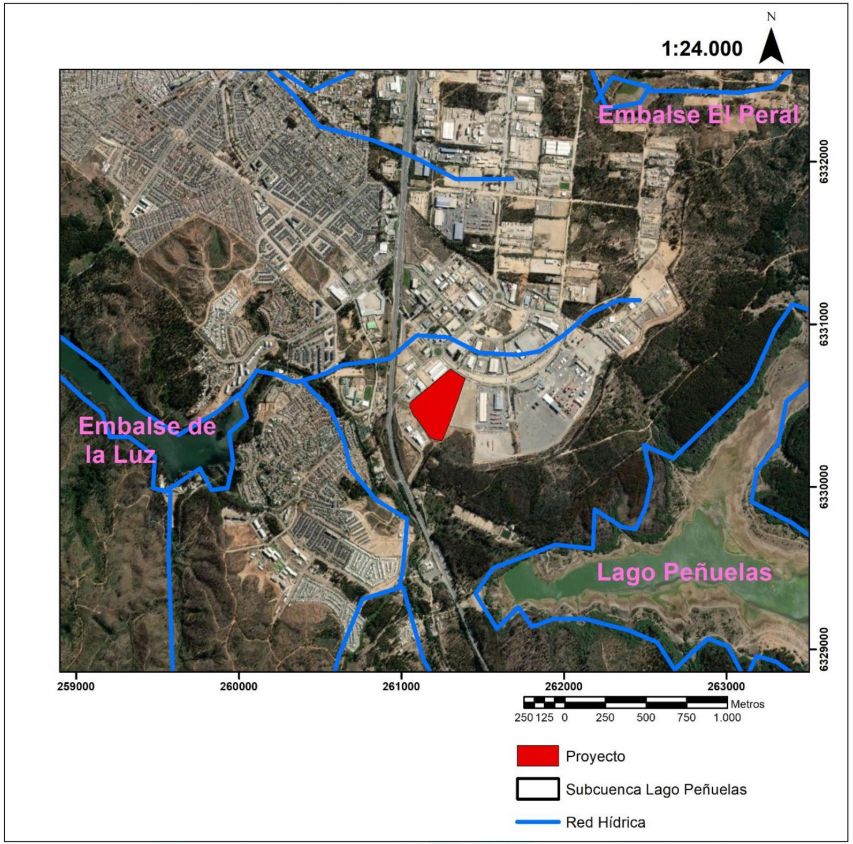

Fuente: Extracto Informe de caracterización hidrológica, Anexo 3.6 de la DIA