Data Center EDCSCL11

Figura 1-1. Ubicación del Proyecto en Datum WGS84

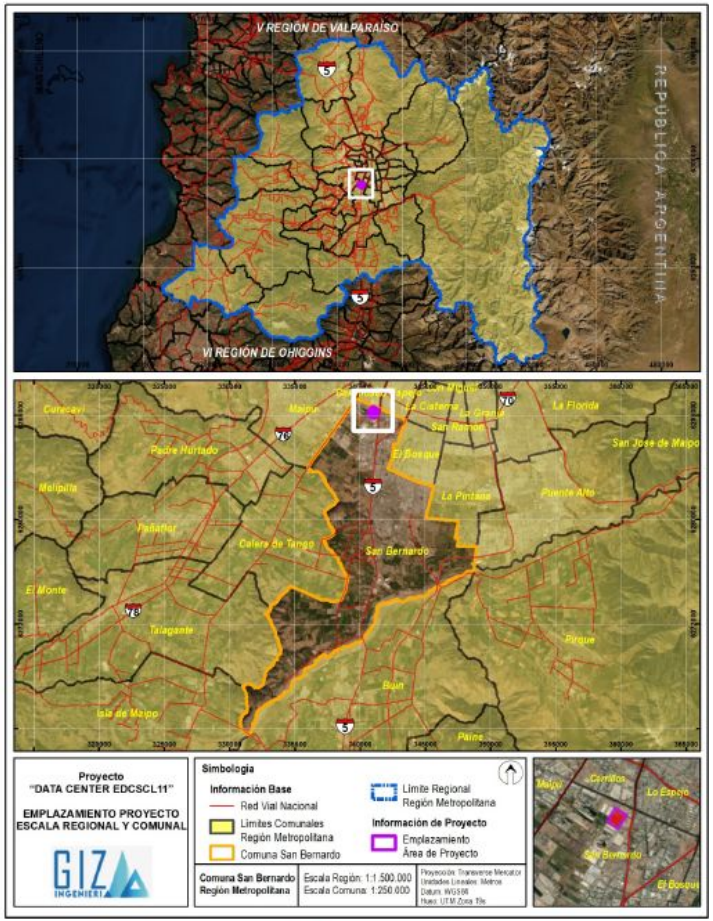

Fuente: Elaboración propia, 2021

Figura 1-2. Acceso al Proyecto.

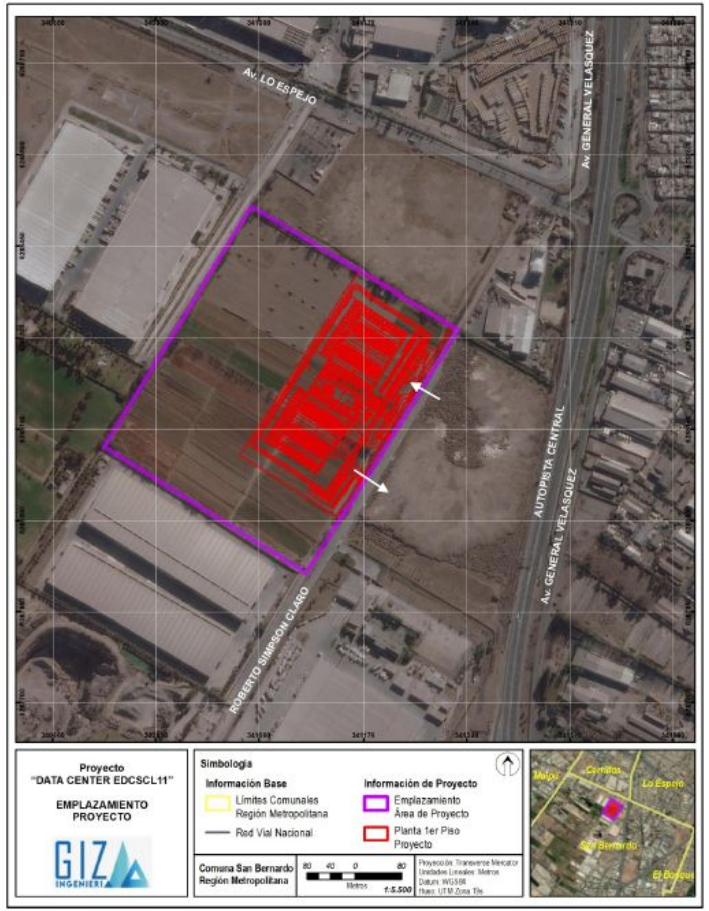

Fuente: Elaboración propia, 2021

Figura 1-3. Detalle del acceso

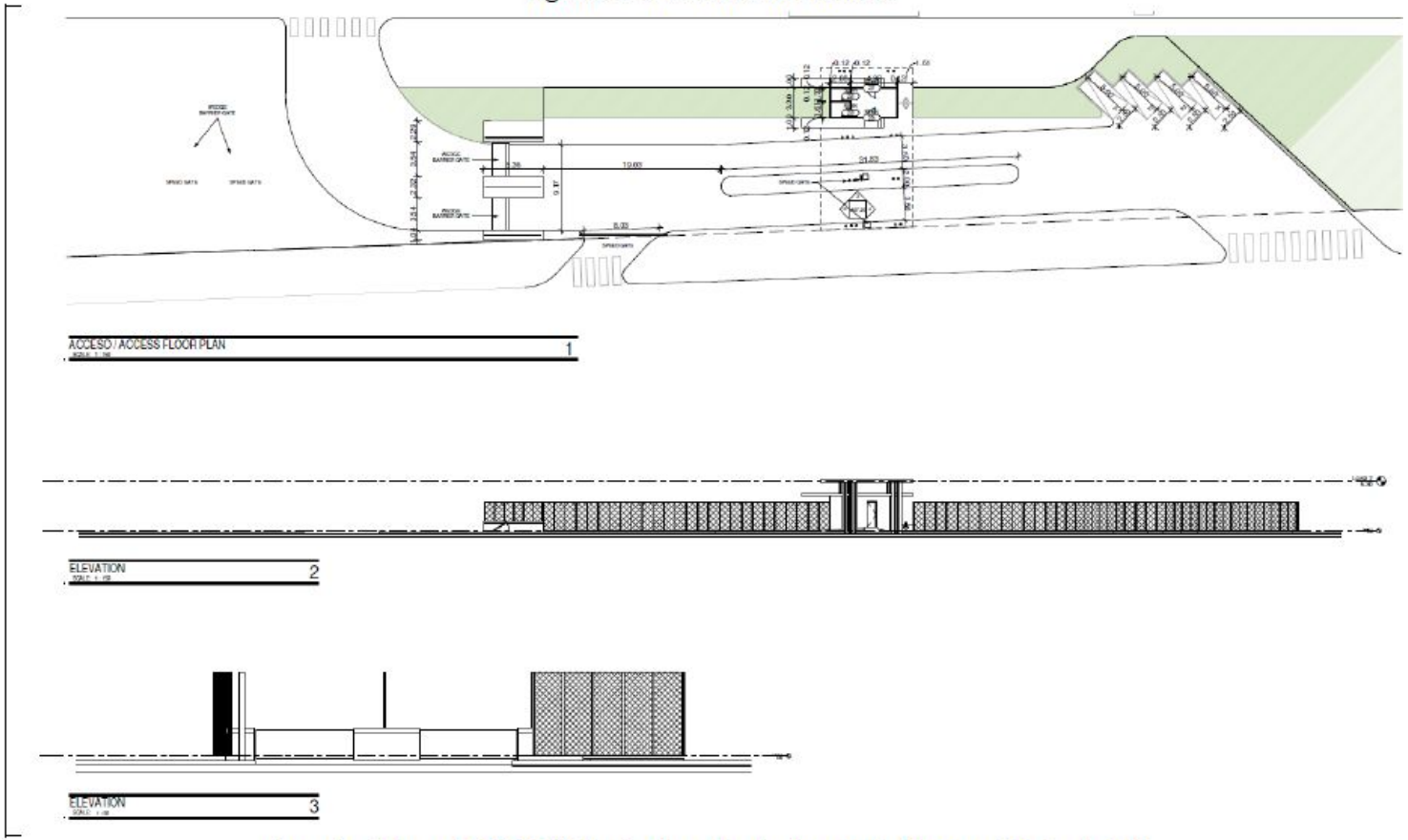

Fuente: Plano A07-20 “Planta Ampliada Acceso”, Anexo 1.3 de la DIA

Figura 1-4. Accesibilidad Universal

Planta 1° accesibilidad universal

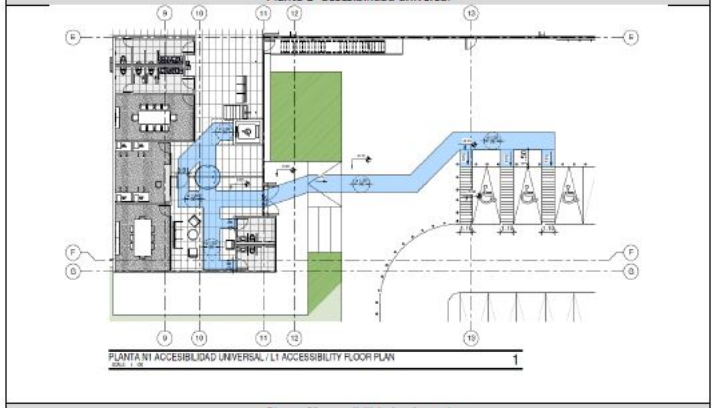

Planta 2° accesibilidad universal

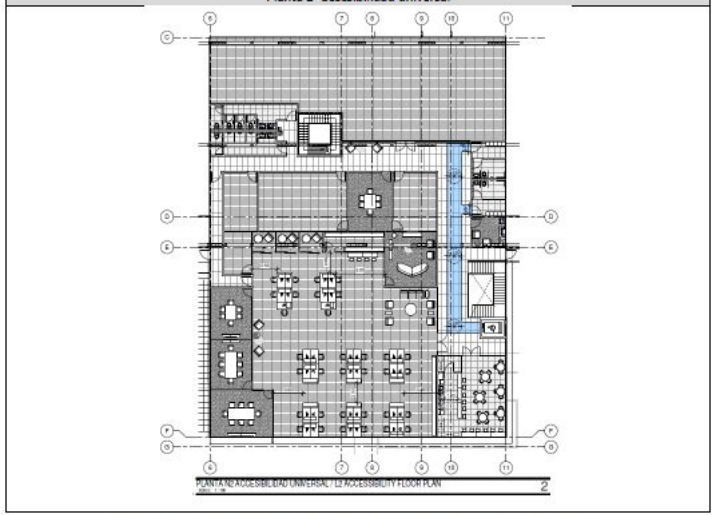

Fuente: Plano A00-07 "Planta Accesibilidad Universal", Anexo 1.3 de la DIA

Figura 1-12. Imágenes del data center



Fuente: Plano A03-00 “Imágenes”, Anexo 1.3 de la DIA

Figura 1-13. Distribución de las partes y obras del Proyecto

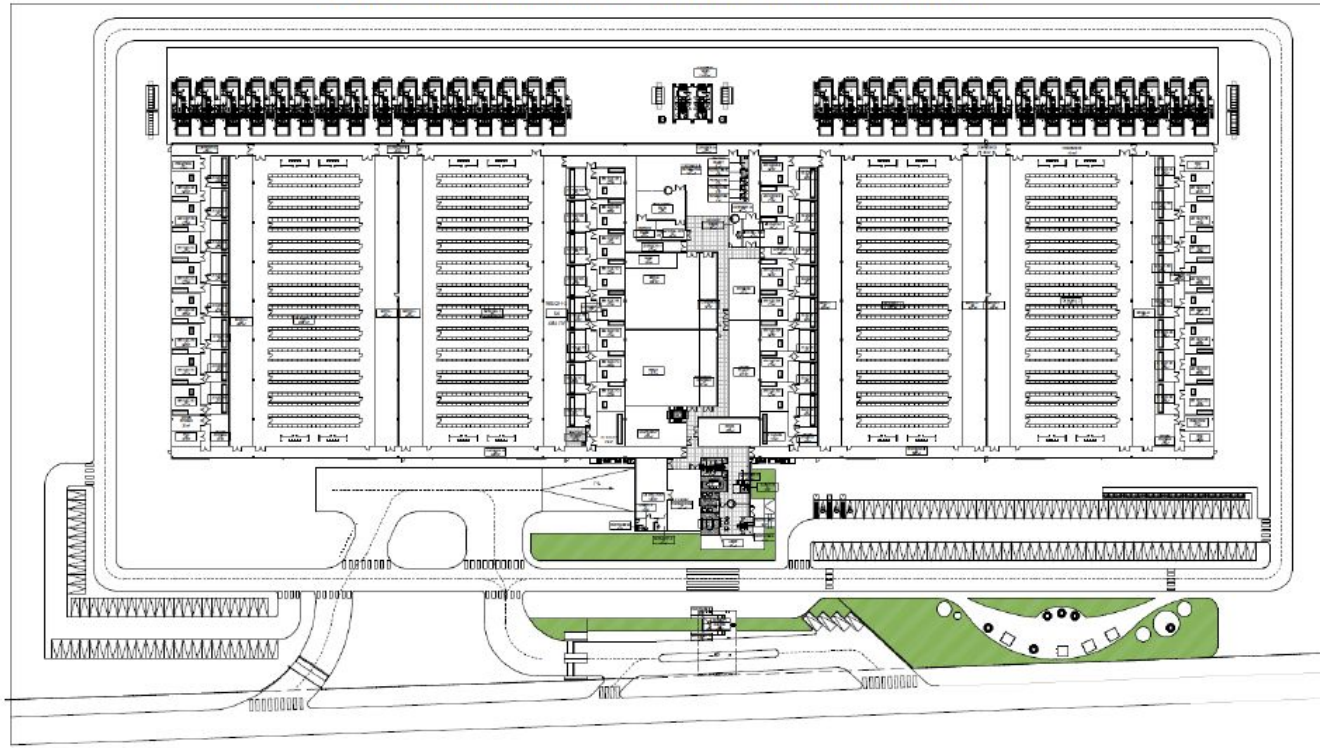

Fuente: Planos de arquitectura, Anexo 1.3 de la DIA

Figura 1-14. Elevaciones

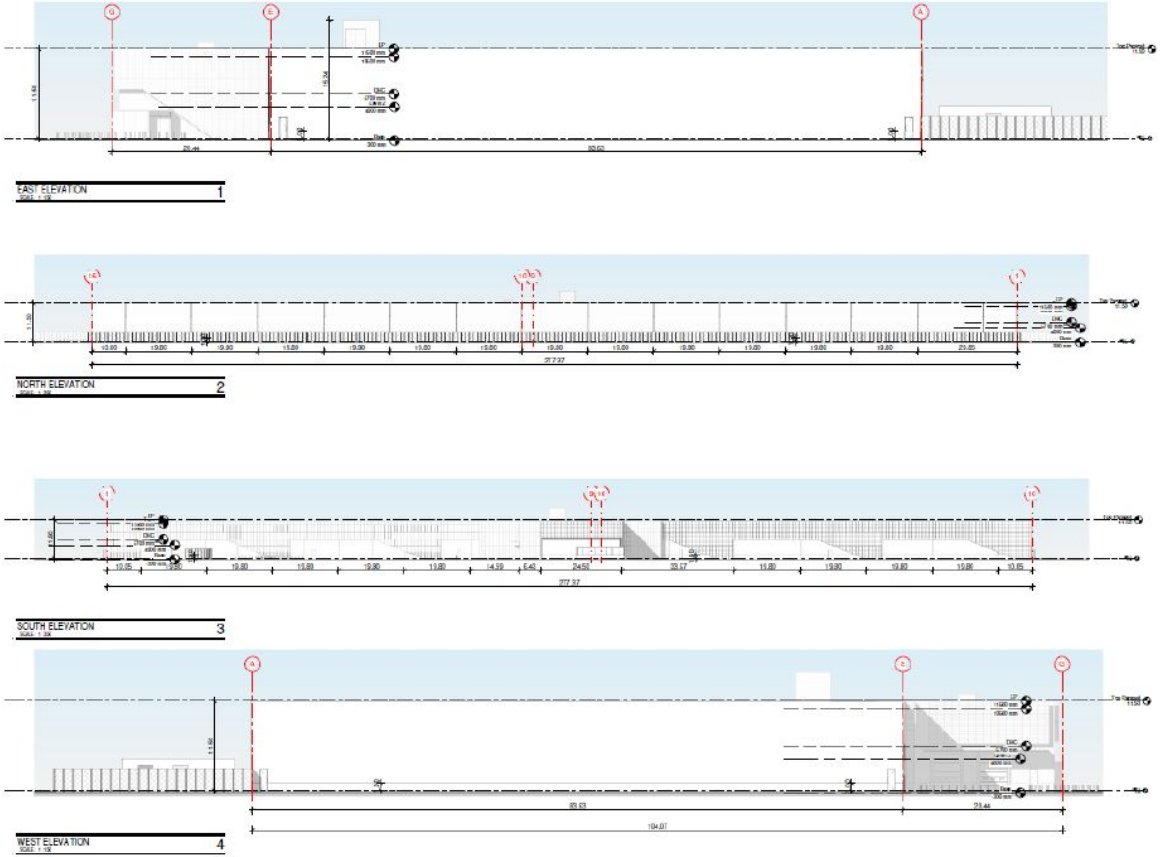

Fuente: Planos de arquitectura, Anexo 1.3 de la DIA

Figura 1-18. Plataforma de equipos electrógenos

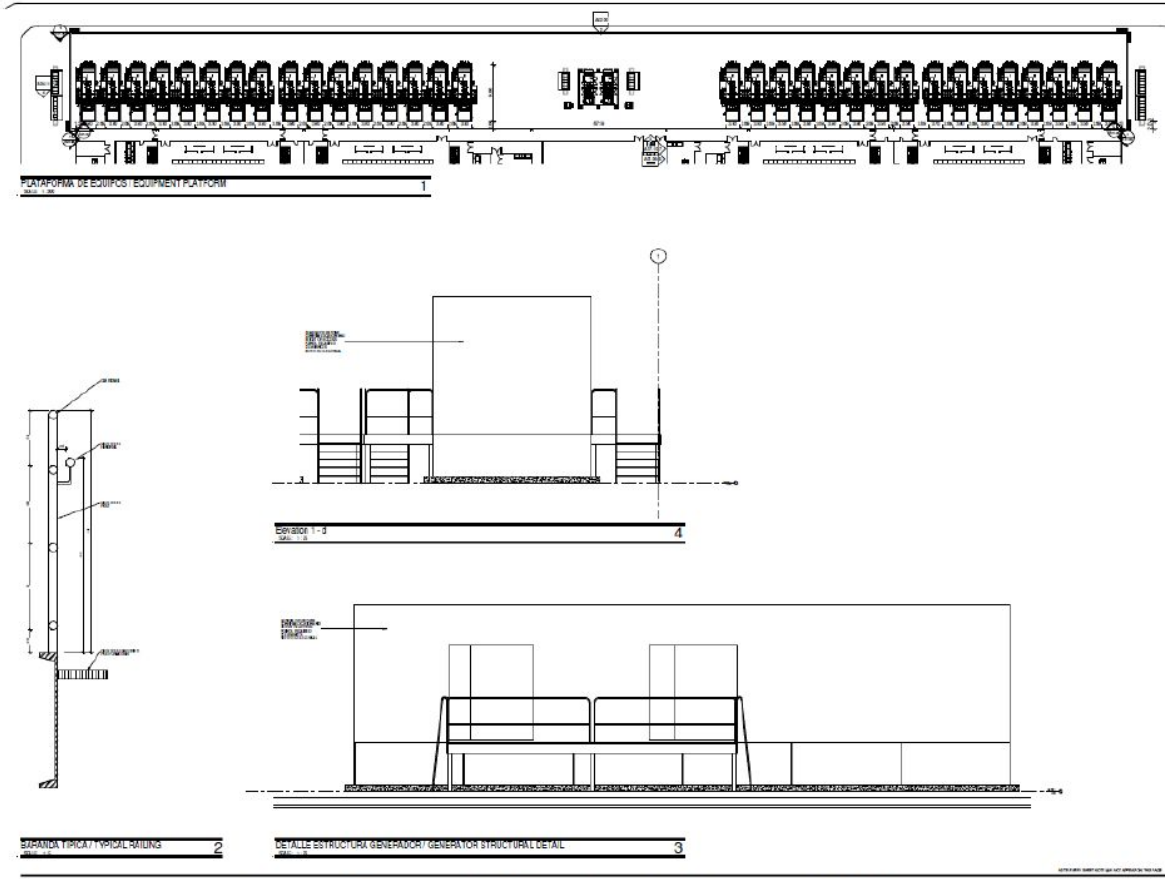

Fuente: Plano A04-11 "Planta de equipos", Anexo 1.3 de la DIA

Figura 1-19. Ventilación en cubierta

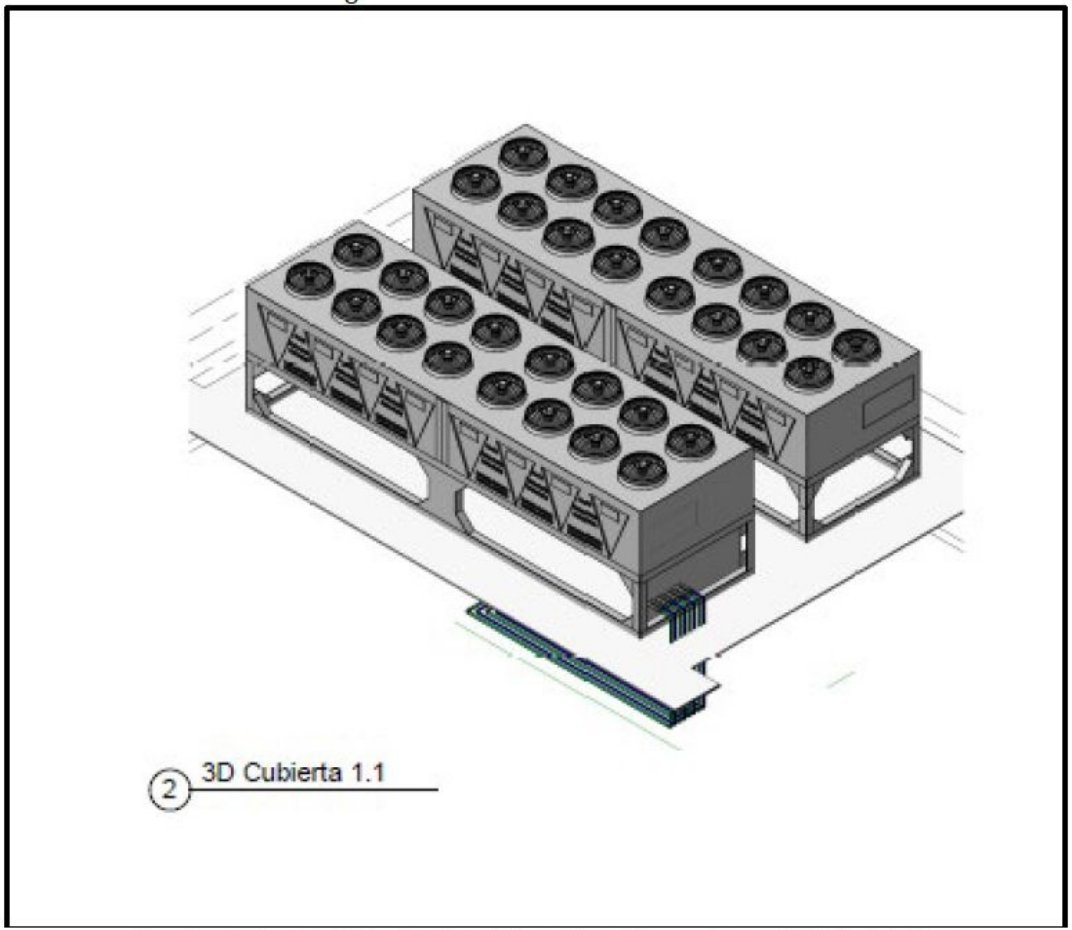

Fuente: Extracto Estudio de ruido y vibraciones, Anexo 1.5 de la DIA

Figura 1-20. Planta cubierta, equipos condensadores

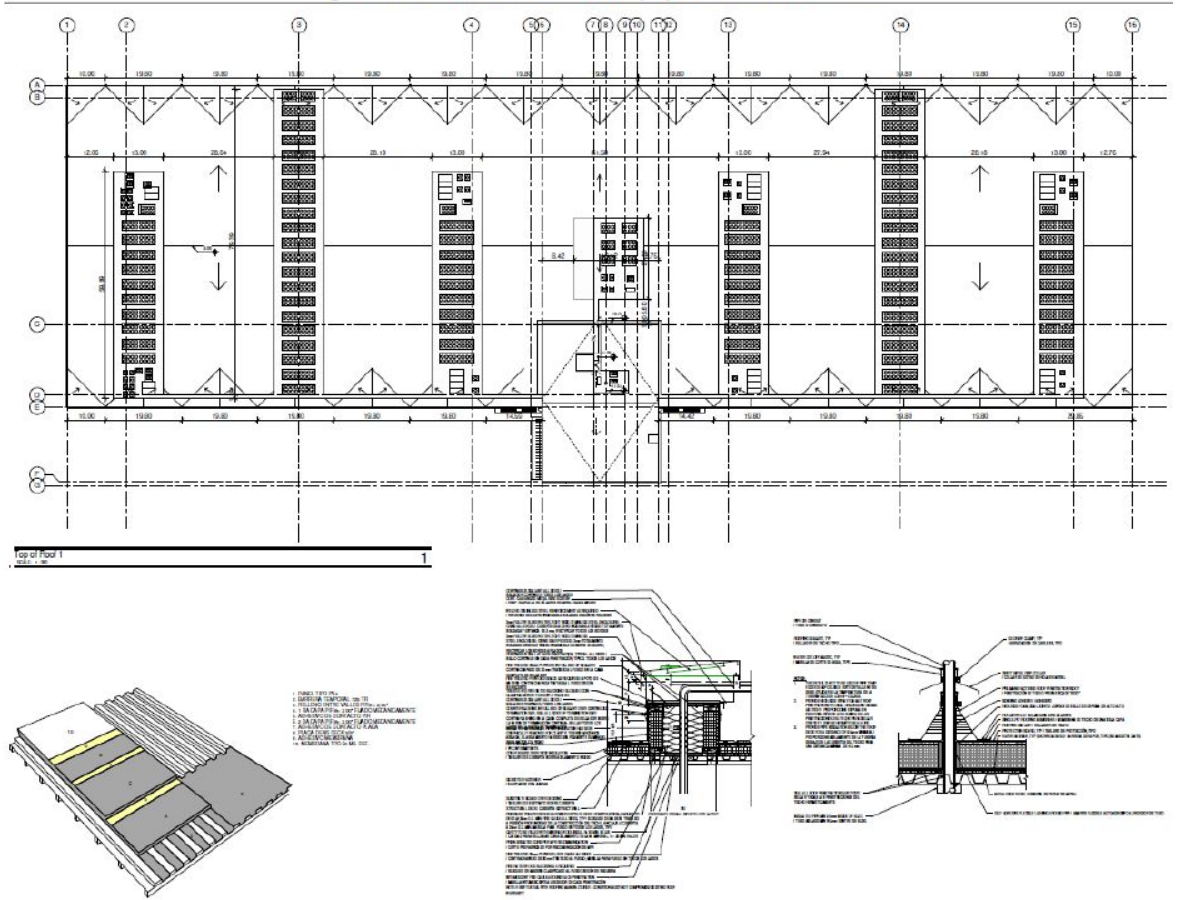

Fuente: Plano A04-16"Planta cubierta", Anexo 1.3 de la DIA

Figura 1-21. Habilitación por fase según sala de datos, N° equipos y sala eletricas.

Habilitación fase 1: puesta en marcha de 8 grupos electrógenos de 2.600 KW, 2 grupos electrógenos de 1.500 KW y 20 condensadores, y además de las oficinas administrativas.

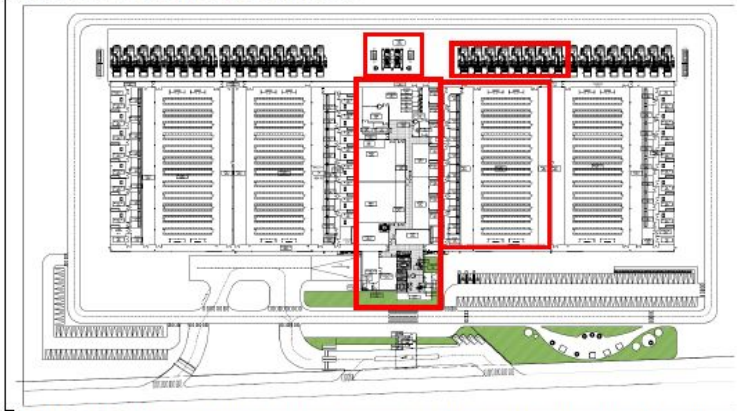

Habilitación fase 2: puesta en marcha de 8 grupos electrógenos de 2.600 KW, 2 grupos electrógenos de 1.500 KW y 20 condensadores.

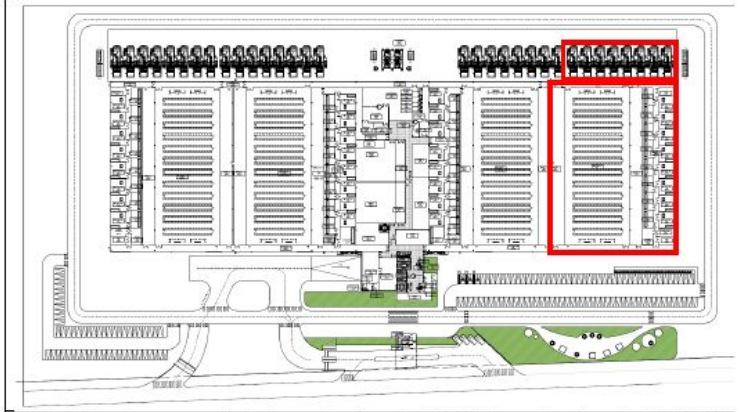

Habilitación fase 3: puesta en marcha de 8 grupos electrógenos de 2.600 KW, 2 grupos electrógenos de 1.500 KW y 20 condensadores.

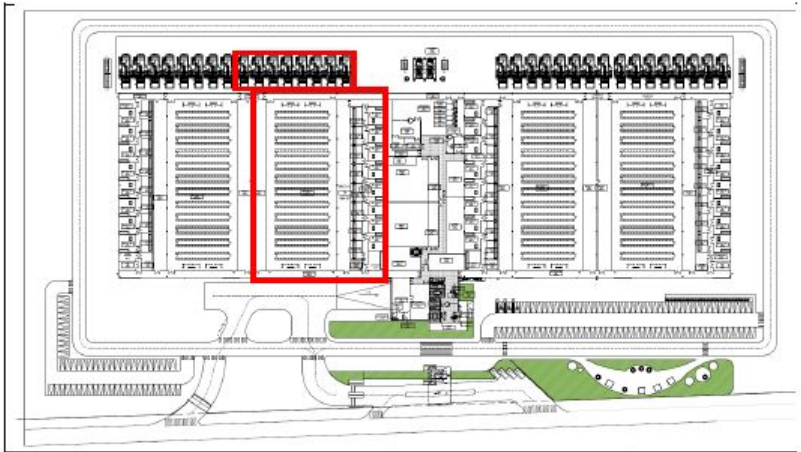

Habilitación fase 4: puesta en marcha de 8 grupos electrógenos de 2.600 KW, 2 grupos electrógenos de 1.500 KW y 20 condensadores.

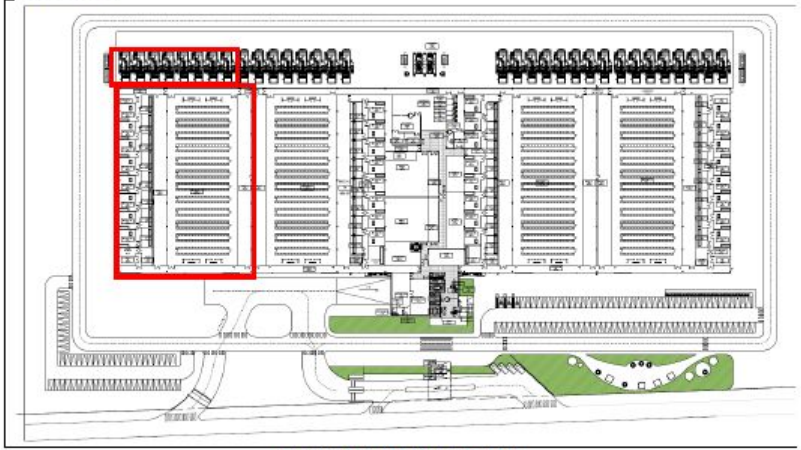

Fuente: Elaboración propia, 2021